Freistaat Bayern, Wasserwirtschaftsamt
Landshuter Straße 59, 93053 Regensburg

Arbeitsgemeinschaft TEAM 3

Anlage F 5.4.1 - Aktualisierung Höhlenbaumerfassung im Eingriffsbereich 2021, 2023 - Fotodokumentation

zum Vorhaben

Neubau Hochwasserschutz
Stadt Regensburg, Abschnitt H Unterer Wöhrd

für den Vorhabensträger	
26.05.2025	
Datum	Unterschrift

Anlage F 5.4.1 Aktualisierung Höhlenbaumerfassung im Eingriffsbereich 2021

Fotodokumentation

127

161

162

163

Anlage F 5.4.1 Aktualisierung Höhlenbaumerfassung im Eingriffsbereich 2021

Fotodokumentation

164

165

166



167

Anlage F 5.4.1 Aktualisierung Höhlenbaumerfassung im Eingriffsbereich 2021

Fotodokumentation

168

169

171

172

Anlage F 5.4.1 Aktualisierung Höhlenbaumerfassung im Eingriffsbereich 2021

Fotodokumentation



173

174

175

177

Anlage F 5.4.1 Aktualisierung Höhlenbaumerfassung im Eingriffsbereich 2021

Fotodokumentation

179

180

181

182

Anlage F 5.4.1 Aktualisierung Höhlenbaumerfassung im Eingriffsbereich 2021

Fotodokumentation

183

185

186

187



188

189

190

191



192

193

195

196

Anlage F 5.4.1 Aktualisierung Höhlenbaumerfassung im Eingriffsbereich 2021

Fotodokumentation

197

198

199

200

Anlage F 5.4.1 Aktualisierung Höhlenbaumerfassung im Eingriffsbereich 2021

Fotodokumentation



202

203

204

206

208

209

210

211

Anlage F 5.4.1 Aktualisierung Höhlenbaumerfassung im Eingriffsbereich 2021

Fotodokumentation

212

213

214



215

Anlage F 5.4.1 Aktualisierung Höhlenbaumerfassung im Eingriffsbereich 2021

Fotodokumentation



216

219

220



221

Anlage F 5.4.1 Aktualisierung Höhlenbaumerfassung im Eingriffsbereich 2021

Fotodokumentation

223

225

226

227

Anlage F 5.4.1 Aktualisierung Höhlenbaumerfassung im Eingriffsbereich 2021

Fotodokumentation

228

229

230

231

Anlage F 5.4.1 Aktualisierung Höhlenbaumerfassung im Eingriffsbereich 2021

Fotodokumentation

232

691-1

691-3

691-5

Anlage F 5.4.1 Aktualisierung Höhlenbaumerfassung im Eingriffsbereich 2021

Fotodokumentation

691-7

704-1

407-2

413-1

413-2

Anlage F 5.4.1 Aktualisierung Höhlenbaumerfassung im Eingriffsbereich 2023

Fotodokumentation

780-(1)



780-(2)

Weidenstrünke-(1)

Weidenstrünke-(2)

Anlage F 5.4.1 Aktualisierung Höhlenbaumerfassung im Eingriffsbereich 2023

Fotodokumentation

Weidenstrünke-(3)

Weidenstrünke-(4)