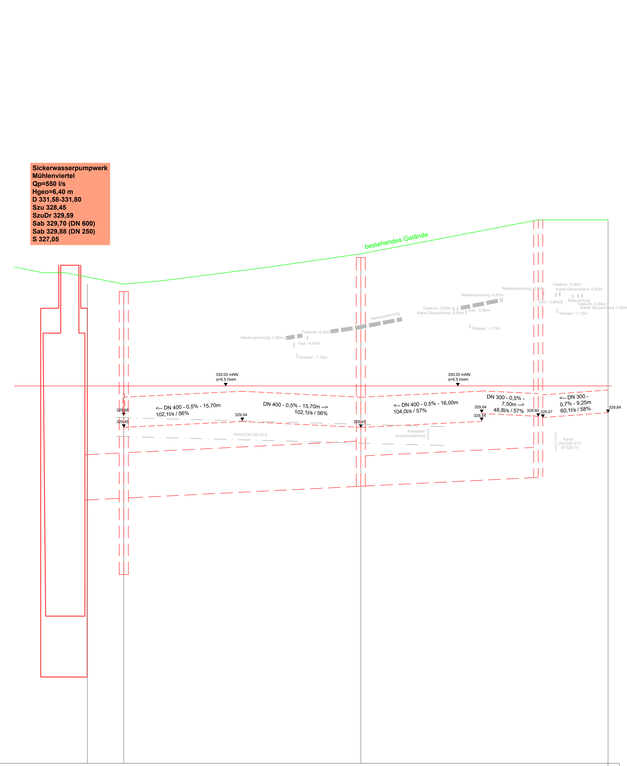

Drainage-West

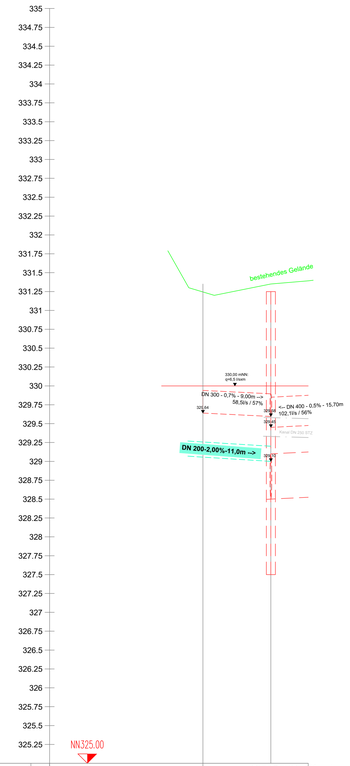

Drainage-Nord

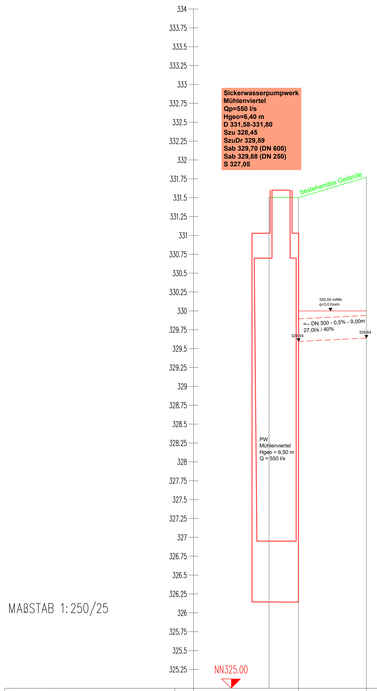

Transportkanal

Schacht-Nr.		S1 Mühl (Sandfang)		S2 Mühl		S3 Mühl	
Straße		Wöhrdstraße					
Haltungslänge	m		5,50	30,90		23,50	
Gesamtlänge	m		38,35			23,50	
Querschnitt / Material	mm		600			400	
Abflußmenge / Abfluß bei Vollfüllung	l/s		475,5 / 559,7		314,9 / 472,5		108,9 / 162,4
Geländehöhe geplant / (bestehend)	mNN	331,600 (331,900)	331,250 (331,550)		331,700 (331,790)	332,200 (332,600)	332,200 (332,200)
Sohlhöhe	mNN	328,45	328,50		328,67	328,80	
Sohlgefälle	‰		7,0	5,0		5,0	
Stationierung	m	68,95	64,10		32,75	9,25	0,00

Schacht-Nr.		S1 Mühl (Sandfang)	
Straße		Wöhrdstraße	
Haltungslänge	m		30,90
Gesamtlänge	m		
Querschnitt / Material	mm		600
Abflußmenge / Abfluß bei Vollfüllung	l/s		314,9 / 472,5
Geländehöhe geplant / (bestehend)	mNN	331,250 (331,550)	
Sohlhöhe	mNN	328,80	
Sohlgefälle	‰		5,0
Stationierung	m	73,10	64,10

Schacht-Nr.			
Straße			
Haltungslänge	m		
Gesamtlänge	m		
Querschnitt / Material	mm		
Abflußmenge / Abfluß bei Vollfüllung	l/s		
Geländehöhe geplant / (bestehend)	mNN	331,600 (331,900)	331,900 (331,790)
Sohlhöhe	mNN		
Sohlgefälle	‰		
Stationierung	m	9,00	0,00

ZEICHENERKLÄRUNG

Planung

- Sickerwasserspenden
- Drainagerohr mit Querschnitt in mm, Sohl-gefälle, Länge, Abflussmenge und Fließsele in Prozent des Querschnitts, Angabe Sohlhöhe
- Transportkanal
- Anschlussleitung für Straßenoberflächenentwässerung

Bestand

- querende Leitungen im Grabenbereich
- Leitungen in Fließrichtung rechts im Grabenbereich
- Leitungen in Fließrichtung links im Grabenbereich

Höhenangaben der Versorgungsleitungen beziehen sich auf das bestehende Gelände und sind Schätzangaben

Vermerke Genehmigungsbehörde :

Wasserwirtschaftsamt Regensburg

STADT REGENSBURG

Index	Bemerkung	geändert am	Name	geprüft am	Name
a					
b					
c					

Übersichtslageplan

Vorhaben :	Hochwasserschutz Regensburg Abschnitt H Unterer Wöhrd PLANFESTSTELLUNG	Plan-Grdl.	36200-E- C 1.2.1
		Anlage: C 1.2.1	Plan-: G
Landkreis/ Stadt :	Regensburg	Plan-Nr.	RB-H- PA4 LS 250
Vorhabensträger :	Freistaat Bayern, Wasserwirtschaftsamt Landshuter Straße 59, 9053 Regensburg	Vorhabensnummer/schlüssel:	G7c 36200/0105
Maßstab : 1:250/25	Planabschnitt : Planabschnitt (PA) 4 Längsschnitt Mühlenviertel	Lagebezug:	GK4 (EPSG 31468)
		Höhenbezug:	Regensburger Höhennetz aus 1927 in ü.NN (4 DHHN12 SU 2016 des LDBV)
Planung :	Arbeitsgemeinschaft TEAM 3	erstle :	3/2024
		gez. :	4/2025
		gepr. :	5/2025
30.04.2025 Datum	Unterschrift Entwurfsverfasser	26.05.2025 Datum	Unterschrift Vorhabensträger

team 3 | Nikolai, SP | WWA