PA 4
SPW Mühlenviertel

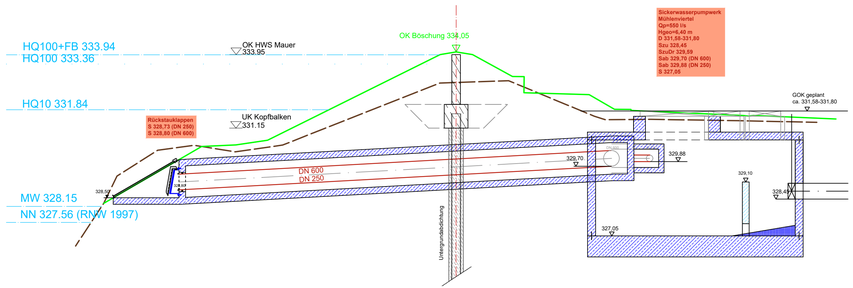

PA 6
Kompaktpumpwerk Werftstraße

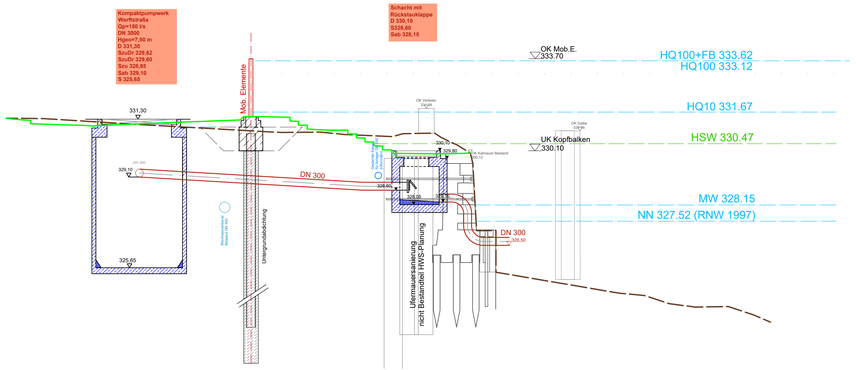

PA 6
SPW Werftstraße

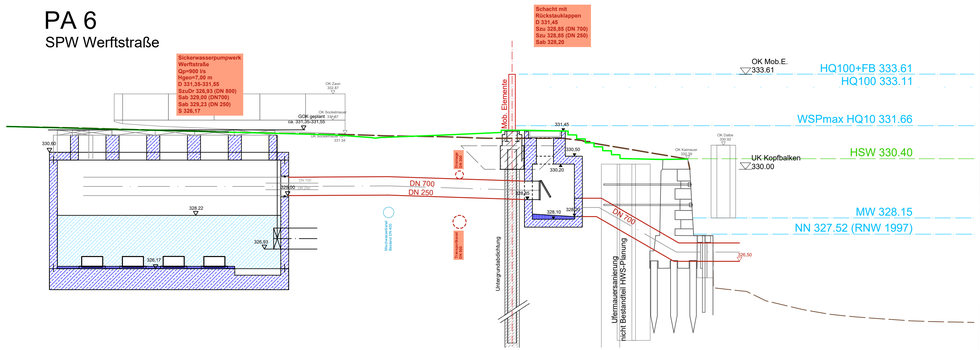

PA 7
SPW Inselstraße

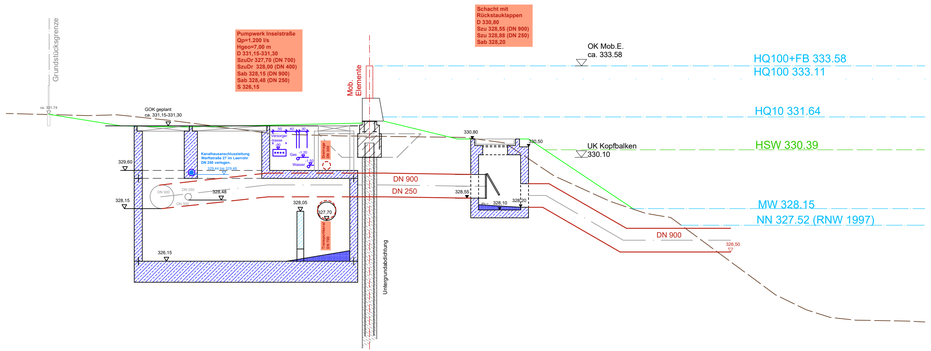

ZEICHENERKLÄRUNG

Planung

- Hochwasserschutzlinie
- DN 25 — Druckleitung mit Dimensionsangabe
- Geländeverlauf

Bestand

- Bestandsgelände

Vermerke Genehmigungsbehörde :

Wasserwirtschaftsamt Regensburg

STADT REGENSBURG

Index	Bemerkung	geändert am	Name	geprüft am	Name
c					
b					
a					

Übersichtslageplan

Vorhaben :	Hochwasserschutz Regensburg Abschnitt H Unterer Wöhrd PLANFESTSTELLUNG	Plan-Code:	36200-E- C 1.3.1
		Anlage : C 1.3.1	Phase : G
Landkreis/ Stadt :	Regensburg	Plan-Nr. :	RB-H- PA4/6/7 S 100
Vorhabensträger :	Freistaat Bayern, Wasserwirtschaftsamt Landshuter Straße 59, 9053 Regensburg	Vorhabenskennzeichen:	G11.9020001015
Maßstab: 1:100	Planinhalt : Planabschnitt (PA) 4/6/7 Schnitte Druckleitung Pumpwerke	Lagebezug:	GK4 (EPSG 31468)
		Höhenbezug:	Regensburger Höhennetz aus 1927 in m ü.NN (# DHHN12/ 92/ 2016 des LDBV)
Planung :	Arbeitsgemeinschaft TEAM 3	entw. :	3/2024 — team 3
		gez. :	3/2024 — Nikolai, SP
		gegr. :	5/2025 — WWA
30.04.2025 Datum	Unterschrift Entwurfsverfasser	26.05.2025 Datum	Unterschrift Vorhabensträger