## Grundriss

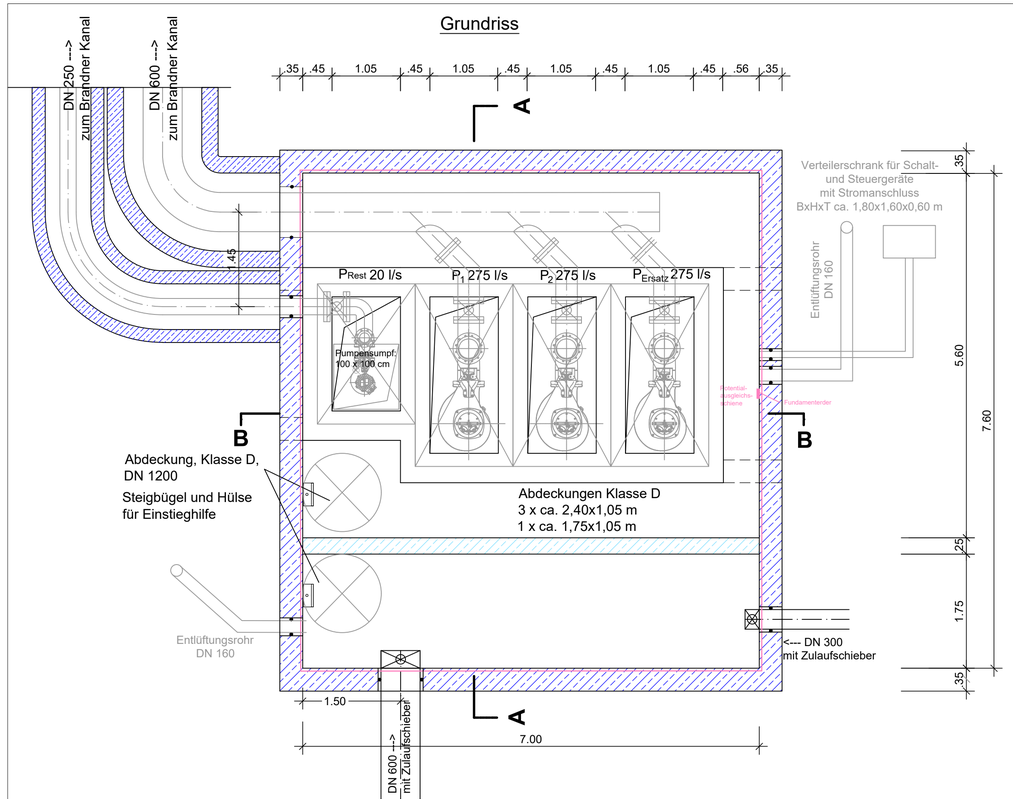


## Rückstauklappen Druckleitungen

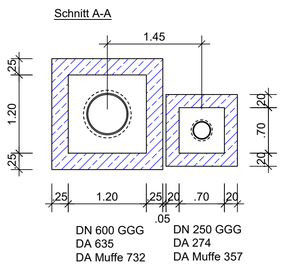


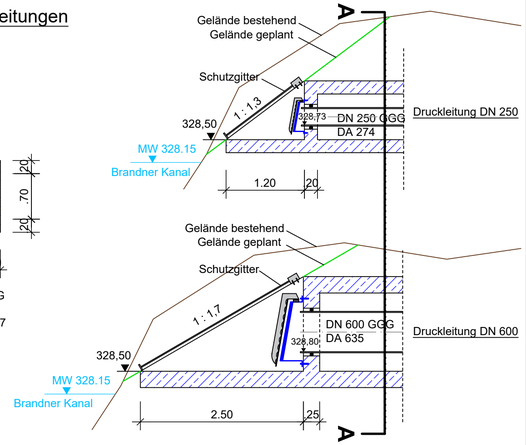


## Schnitt A-A

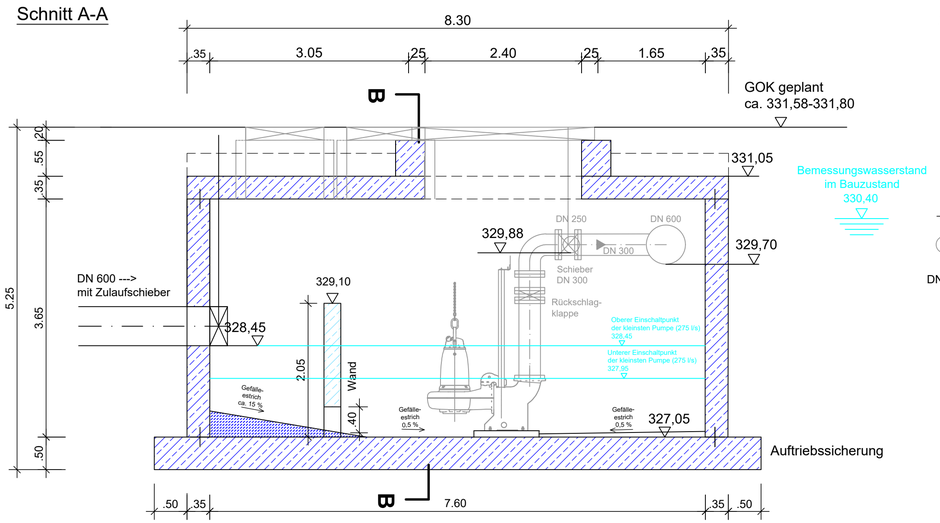


## Schnitt B-B

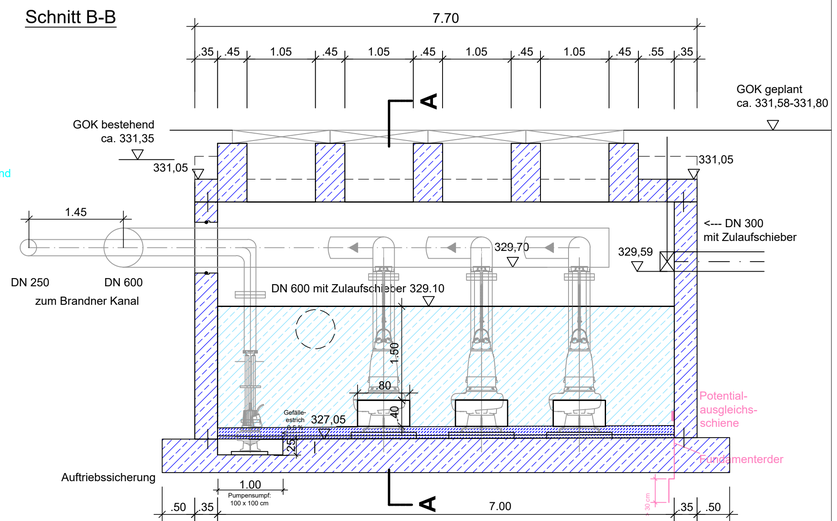


Vermerke Genehmigungsbehörde :

Wasserwirtschaftsamt Regensburg

STADT REGENSBURG

| Index | Bemerkung | geändert am | Name | geprüft am | Name |
|---|---|---|---|---|---|
| c | | | | | |
| b | | | | | |
| a | | | | | |

Übersichtslageplan

| | | | |
|---|---|---|---|
| Vorhaben : | Hochwasserschutz Regensburg<br>Abschnitt H Unterer Wöhrd<br>PLANFESTSTELLUNG | Plan-Code : | 36200-E- C 4 |
| | | Anlage : C 4 | Phase : G |
| Landkreis/ Stadt : | Regensburg | Plan-Nr. : | RB-H- PA4 SPW 50 |
| Vorhabensträger : | Freistaat Bayern, Wasserwirtschaftsamt<br>Landshuter Straße 59, 9053 Regensburg | Vorhabenskennzeichen: | G1l 3620001015 |
| Maßstab : 1:50 | Planinhalt : Planabschnitt (PA) 4<br>Sickerwasserpumpwerk Mühlenviertel | Lagebezug: | GK4 (EPSG 31468) |
| | | Höhenbezug: | Regensburger Höhennetz aus 1927 in m ü.NN (# DHHN12/ 92/ 2016 des LDBV) |
| Planung : | Arbeitsgemeinschaft TEAM 3<br>Schönigplan Ingenieurgesellschaft mbH · Archiscape architekten und landschaftsarchitekten · ymr. Landschaftsarchitekten | entw. : | 3/2024 team 3 |
| | | gez. : | 3/2024 Nikolai, SP |
| | | gepr. : | 5/2025 WWA |
| 30.04.2025 Datum | Unterschrift Entwurfsverfasser | 26.05.2025 Datum | Unterschrift Vorhabensträger |