PA 7

Schacht 3724032A

DN 1.000

Grundriss

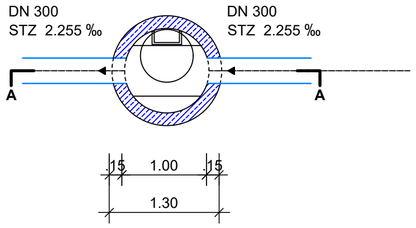

Schnitt A-A

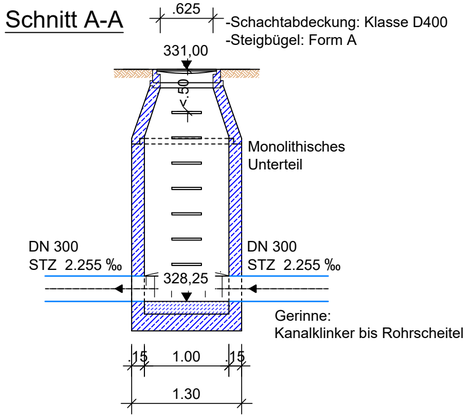

Schacht 3724046A

DN 1.000

Grundriss

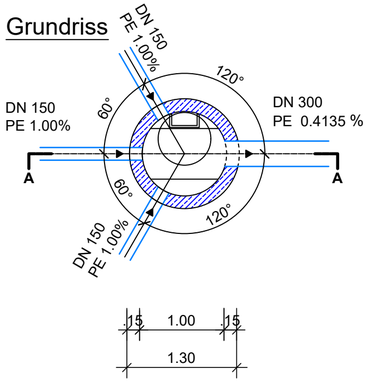

Schnitt A-A

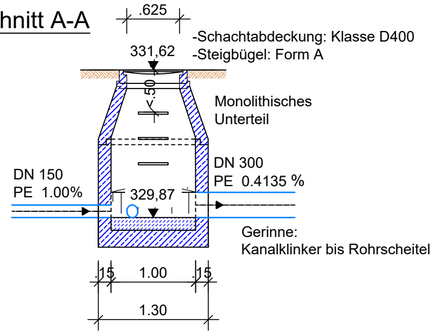

Schacht 372404A

DN 1.000

Grundriss

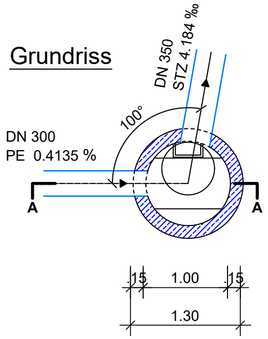

Schnitt A-A

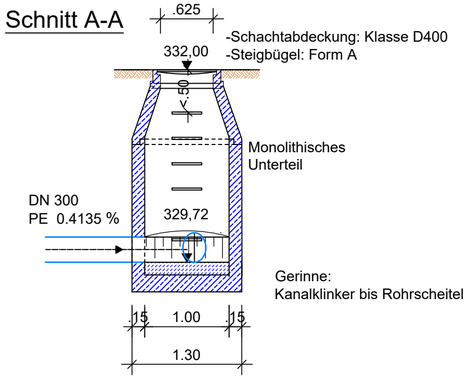

Vermerke Genehmigungsbehörde :

Wasserwirtschaftsamt Regensburg

STADT REGENSBURG

Index	Bemerkung	geändert am	Name	geprüft am	Name
c					
b					
a					

Übersichtslageplan

Vorhaben :	Hochwasserschutz Regensburg Abschnitt H Unterer Wöhrd PLANFESTSTELLUNG	Plan-Code :	36200-E- C 8.8
		Anlage : C 8.8	Phase : G
Landkreis/ Stadt :	Regensburg	Plan-Nr. :	RB-H- PA7 KS 50
Vorhabensträger :	Freistaat Bayern, Wasserwirtschaftsamt Landshuter Straße 59, 9053 Regensburg	Vorhabenskennzeichen:	G1t 3620001015
Maßstab : 1:50	Planinhalt : Planabschnitt (PA) 7 Schachtbauwerke Mischwasserkanal	Lagebezug:	GK4 (EPSG 31468)
		Höhenbezug:	Regensburger Höhennetz aus 1927 in m ü.NN (≠ DHHN12/ 92/ 2016 des LDBV)
Planung :	Arbeitsgemeinschaft TEAM 3 schömigplan INGENIEURGESELLSCHAFT mbH · archiscape architekten und landschaftsarchitekten · gm. Landschaftsarchitekten	entw. : 3/2024	team 3
		gez. : 3/2024	Nikolai, SP
		gepr. : 5/2025	WWA
30.04.2025 Datum	Unterschrift Entwurfsverfasser	26.05.2025 Datum	Unterschrift Vorhabensträger