Vorhaben:
Hochwasserschutz Regensburg – Abschnitt H / Unterer Wöhrd

Auftraggeber: Planer / örtl. BÜ: Auftragnehmer Bau:	WWA Regensburg Team 03

Beratungstermin Fachbeitrag EU-Wasserrahmenrichtlinie	58	Ort: Video-Konferenz Datum: **14.04.2022** Uhrzeit: 10:00 – 11:30

Teilnehmer:

			Verteiler
Herr Zimmermann, WWA	rainer.zimmermann@wwa-r.bayern.de	0941 / 78009- 128	☒
Herr Bertram, WWA	bertram.tobias@wwa-r.bayern.de	0941 / 78009- 209	☒
Herr Dr. Brandner, WWA	Joerg.Brandner@wwa-r.bayern.de		☒
Herr Bulla, WWA	Andreas.Bulla@wwa-r.bayern.de		☒
Herr Graml, WWA	Maximilian.Graml@wwa-r.bayern.de		☒
Frau Pollinger, WWA	Christine.pollinger@wwa-r.bayern.de	0941 / 78009- 114	☒
Herr Völkel, WWA	Fabian.voelkel@wwa-r.bayern.de		☒
Anwärterinnen, WWA			
Herr Dr. Becker, bgmr	becker@bgmr.de	030 / 2145959-0	☒
Frau Hain, bgmr	hain@bgmr.de	030 / 2145959-17	☒
Herr Mackenrodt, archiscape	mackenrodt@archiscape.de	030 / 532163- 50	☒
Herr Karmann, Schömig-plan	karmann@schoemig-plan.de	06027 / 504- 217	☒
Herr Plötz, UA, SG Wasserrecht (Planfeststellungsbehörde)	ploetz.markus@regensburg.de	0941 / 507 – 1710	☒
Frau Dr. Pöhler, UA, Untere Naturschutzbehörde	Poehler.Hannaleena@regensburg.de	0941 / 507 - 1643	☒

Anlagen: 20220414_HWS-H_Termin FB EU-WRRL, Stand 14.04.2022

Anlass und Ziel der Beratung:
Der Termin dient der Klärung des Untersuchungsrahmens für die Erstellung eines Fachbeitrags EU-Wasserrahmenrichtlinie im Rahmen des Hochwasserschutzprojektes Unterer Wöhrd.

Die Ergebnisse sind im Folgenden zusammengefasst:

TOP	*Tagesordnungspunkt*	*zuständig*	*Termin*
1	**Begrüßung / Einführung, Anlass** Herr Zimmermann begrüßt die Anwesenden. Die Teilnehmenden stellen sich vor. Herr Zimmermann erläutert den Prozess der Ermittlung des Prüfbedarfs zur Erstellung eines Fachbeitrags EU-Wasserrahmenrichtlinie (FB EU-WRRL) für das Vorhaben. Von ministerieller Seite wird die Erstellung eines solchen Fachbeitrags als Teil der Planfeststellungsunterlagen als formal notwendig erachtet. Der FB EU-WRRL wird der erste Fachbeitrag dieser Art für Hochwasserschutzmaßnahmen (HWS) in Regensburg sein. Bis zur Einleitung des letzten Planfeststellungsverfahrens für den HWS im Jahr 2017 war die Erstellung eines solchen FB noch nicht notwendig.		
2	**Kurzvorstellung Stand Entwurfsplanung HWS-H** Frau Hain stellt den aktuellen Planungsstand der HWS-Maßnahmen kurz vor und betont die Aspekte, die für die Bearbeitung des FB EU-WRRL von Bedeutung sind: - Errichtung von HWS-Elementen in der Donauaue (Donau: Flusswasserkörper nach EU-WRRL) - Herstellung einer Untergrundabdichtung im Bereich eines Grundwasserkörpers nach EU-WRRL (Veränderung der Korrespondenz zwischen Grundwasserkörper und Flusswasserkörper) - Bauzeitlicher Eingriff zur Herstellung der Untergrundabdichtung im Bereich eines Flusswasserkörpers (Trockenlegung Mühlenkanal) - Bau und Betrieb von Binnendrainage und Pumpwerken mit Veränderung Hochwasserableitung und Niederschlagsabführung im Starkregenfall Die naturnahe Ufer- und Auenumgestaltung in PA 10 hat positive Wirkungen und setzt Ziele und Maßnahmen des Umsetzungskonzeptes für den Flusswasserkörper Donau 1_F348 um. Bauzeitlich sind temporäre nachteilige Wirkungen zu erwarten.		
3 3.1 3.2	**Fachbeitrag EU-WRRL** Frau Hain erläutert die rechtlichen, fachlichen und methodischen Grundlagen zur Erstellung eines FB EU-WRRL. Das Vorhaben betrifft: - den Grundwasserköper (GWK) 1_G083 Quartär – Regensburg - den Flusswasserkörper (FWK) 1_F348 Donau von Einmündung Naab bis Einmündung Große Laber Frau Hain stellt den IST-Zustand der beiden Wasserkörper im Vorhabenbereich gemäß den Ausführungen der Gewässersteckbriefe in einem Kurzüberblick dar.		

TOP	*Tagesordnungspunkt*	*zuständig*	*Termin*
3.3	Das methodische Vorgehen bei der Beurteilung der Auswirkungen des Vorhabens auf den betroffenen Flusswasserkörper und den betroffenen Oberflächenwasserkörper wird anhand zweier Prüfschemata gemäß LAWA kurz erläutert.		
4	**Zusammenfassung / Diskussion**		
4.1	Frau Hain fasst die Ergebnisse der vorherigen Ausführungen zusammen. Nach einer vorläufigen Ersteinschätzung ist nicht davon auszugehen, dass die Erheblichkeitsschwelle bezüglich der Beeinträchtigung der Bewirtschaftungsziele nach EU-WRRL überschritten wird. Für den FWK 1_F348 wird das Vorhaben sogar eine Verbesserung im HWS-Abschnitt PA 10 erzielen. Eine finale Einschätzung ist nach Vorlage der Ergebnisse der Grundwassermodellierung sowie der Hydraulischen Modellierung möglich.		
4.2	Frau Hain bittet um Hinweise und Ergänzungen und fragt nach Geofachdaten zur Lage der Messstellen und zur Abgrenzung von FWK und GWK. <u>Ergebnisse der Diskussion:</u> Herr Zimmermann wünscht seitens des AG einen möglichst kurz gehaltenen FB EU-WRRL, da einige Inhalte und weiterführende Details zum Thema Wasser auch im Landschaftspflegerischen Begleitplan enthalten sind. Herr Dr. Brandner bittet um Beachtung formaler Aspekte, insbesondere der Verwendung der korrekten Nomenklatur bei der Erstellung des FB EU-WRRL. Dazu gehört die korrekte Bezeichnung der FWK-Kennung: 1_F348 statt 1_348 (Präsentation anpassen). Der Ort der Beurteilung ist für den FWK die „operative“ Messstelle bzw. die „operativen“ Messstellen (= repräsentative Messstellen). Herr Zimmermann wagt die These, dass mit sehr großer Sicherheit davon auszugehen ist, dass das Vorhaben keine negativen Auswirkungen auf die Wasserkörper nach EU-WRRL haben wird. Herr Dr. Brandner ergänzt, dass das Vorhaben für den FWK 1_F348 sogar positive Wirkungen erzeugt (Verbesserung der Hydromorphologie in PA 10). Lediglich bauzeitlich sind nachteilige Wirkungen möglich (Trockenlegung Mühlenkanal). Aber hierfür können gemäß Frau Hain Vorkehrungen getroffen werden. Entsprechende Vermeidungs- und Minderungsmaßnahmen sind bereits in der speziellen artenschutzrechtlichen Prüfung (saP) und dem Landschaftspflegerischen Begleitplan (LBP) formuliert worden. Bezüglich der Auswirkungen auf den Grundwasserkörper 1_G083 sind gemäß Herrn Bulla keine relevanten Veränderungen zu erwarten. Die Auswirkungen durch die Untergrundabdichtungen sind nur lokal und werden keine nennenswerten negativen Auswirkungen auf den Grundwasserkörper in seiner Gesamtheit haben. Die Hauptprobleme für den GWK sind qualitativer Art und werden durch Schadstoffeinträge (Nitrat, PSM) aus der Landwirtschaft verursacht. Im Ergebnis dieser Einschätzungen wird der Untersuchungsrahmen für den FB EU-WRRL auf die Durchführung einer Vorprüfung festgelegt. Die textlichen Ausführungen sind möglichst kurz zu halten.	*bgmr*	

TOP	*Tagesordnungspunkt*	*zuständig*	*Termin*
	Ergänzungen zu fachlichen Vorgaben, Vollzugshinweisen etc. werden seitens der Teilnehmenden nicht benannt. Die durch bgmr dargestellte Grundlagenrecherche wird als ausreichend erachtet. Im Nachgang des Termins können Fragen zur Methodik und zum FWK an Herrn Dr. Brandner und zum GWK an Herrn Bulla gestellt werden. Eine Datenabfrage zu Grund- und Oberflächenwasserkörper und Messstellen kann bei Herrn Anton Frai (Tel. 0941 78009-302) erfolgen.		

Nächster Termin: für das Thema Fachbeitrag EU-WRRL ist kein weiterer Beratungstermin vorgesehen.

(Erstellt: Team 3 – Team3 am 14.04.2022 / Freigabe WWA am 08.08.2022)

Fachbeitrag EU-Wasserrahmenrichtlinie (WRRL)

Beratung

14.04.2022

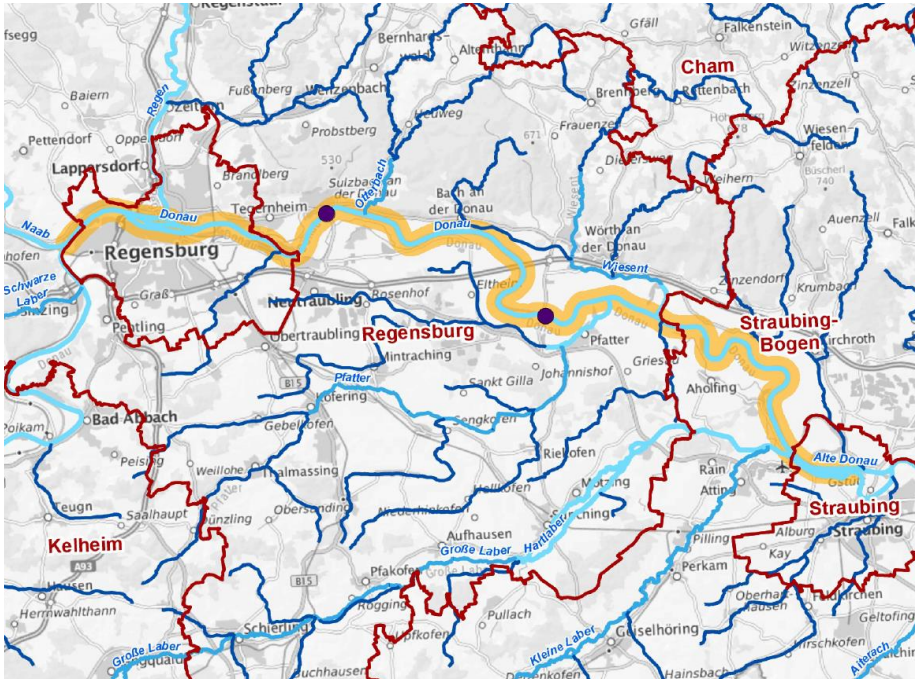

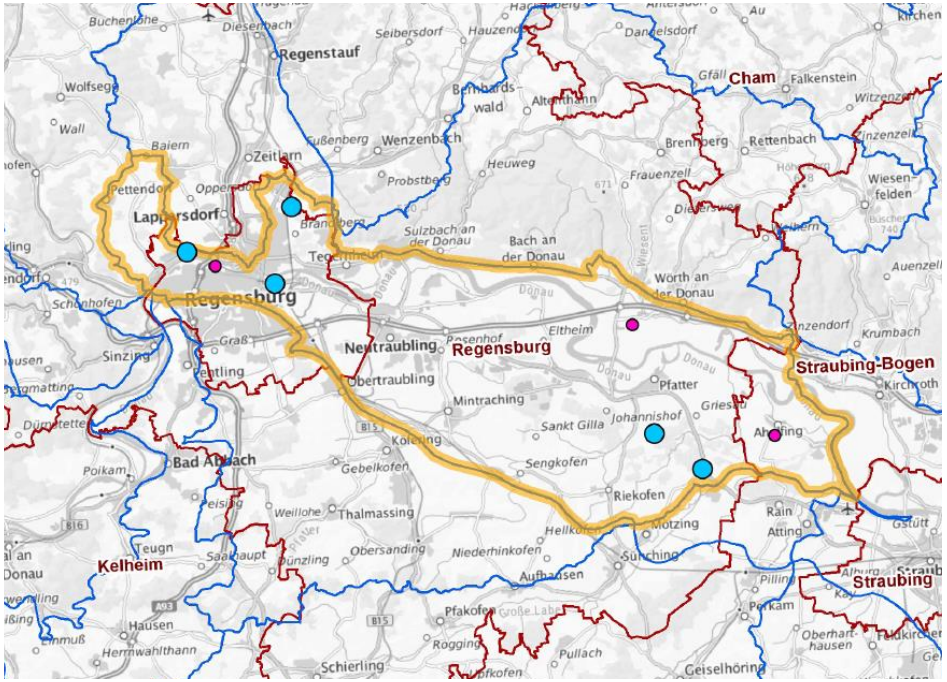

Vorstellung Team 3

Interdisziplinäres Team aus Architekten und Landschaftsarchitekten/
Landschaftsplanern, Bauingenieuren, Geologen, Vermessern

Für Fachbeitrag EU-WRRL sowie weitere umwelt- und naturschutzfachliche Planungen und Prüfungen:

bgmr. Landschafts architekten

Dr. Carlo Becker
Dipl. Ing. Tanja Hain

bgmr Landschaftsarchitekten GmbH
Prager Platz 6
10779 Berlin
Tel 030. 214 5959-0
hain@bgmr.de

Inhalt

1. Einführung | Anlass
2. Kurzvorstellung Stand Entwurfsplanung HWS-H
3. Fachbeitrag EU-WRRL – rechtliche, fachliche, methodische Grundlagen
4. Fachbeitrag EU-WRRL – IST-Zustand Wasserkörper im Vorhabenbereich
5. Vorgehen bei der Bearbeitung des Fachbeitrages
6. Zusammenfassung
7. Diskussion

Einführung | Anlass

Hochwasserschutzmaßnahmen dienen dem Schutz von Menschen

Sie sind jedoch komplex und können in ihrer Anlage, ihrer baulichen Ausführung und der betrieblichen Nutzung auch nachteilige Wirkungen auf Grund- und Oberflächen-wasserkörper gemäß EU-WRRL haben.

Team 3: Vorabzug Entwurf PA 1-7,
Stand: Nov. 2021

→ Vorhaben erzeugt Veränderungen im Bereich eines Flusswasserkörpers und eines Grundwasserkörpers nach EU-WRRL.

→ Notwendigkeit zur Erstellung eines FB EU-WRRL durch WWA geprüft und bestätigt.

HWS-H Maßnahme: Stand der Entwurfsplanung

Übersichtsplan HWS-H, PA 1-7

Team 3: Vorabzug Entwurf PA 1-7,
Stand: Nov. 2021

Rote Linie: oberirdischer HWS, z.T. Untergrundabdichtung

Bauzeitlich temporäre
Trockenlegung Mühlenkanal

- Oberirdischer HWS in Donauaue: HWS-Mauern, -tore, mobile Elemente, Deich mit integrierter HWS-Wand, Geländeanhebungen; Trafostationen mit Leitungen
- Untergrundabdichtung im Grundwasserkörper: U-Lösung, vertikal, z.T. horizontal
- Binnendrainage, Pumpwerke: Veränderung Hochwasser-Ableitung, Niederschlagsabführung

HWS-H Maßnahme: Stand der Entwurfsplanung

Lage HWS-Linie, Binnendrainage, Pumpwerke, Einleitungen in Donau

Team 3: Vorabzug Entwurf,
Stand: Dez. 2021

HWS-H Maßnahme: Stand der Entwurfsplanung

Lage Untergrundabdichtung (Auszug aus Grundwassermodellierung)

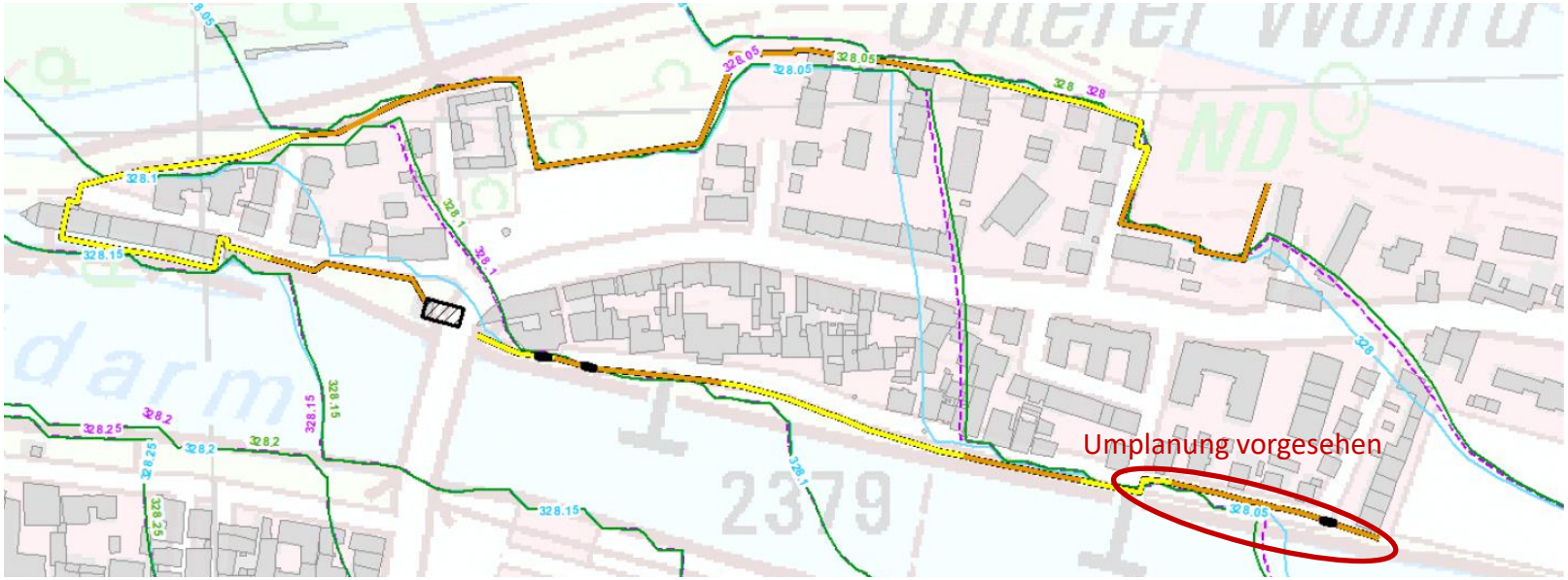

Quelle: Ausschnitt ppt BCE (Jan. 2022)

Vertikale Untergrundabdichtung: U-Lösung
>> Auswirkungen auf GWK, FWK (Mühlenkanal) und Verbindung zwischen FWK/GWK

HWS-H Maßnahme: Stand der Entwurfsplanung

Vorabzug Entwurf PA 10: Naturnahe Ufer- und Auenumgestaltung

Entwurf Team 3: Vorabzug, Stand Dez. 2021

- Umsetzung von Zielen und Maßnahmen des Flussraumkonzeptes
- Umsetzung Kompensationsmaßnahmen für Eingriffe in Natur und Landschaft (LBP)
- Umsetzung von Zielen und Maßnahmen des Umsetzungskonzeptes FWK Donau 1_F348

>> positive Wirkungen auf ökologischen Zustand FWK, die Hydromorphologie (Gewässerstrukturgüte)

FB EU-WRRL - Grundlagen

Rechtliche Vorgaben

EU-Wasserrahmenrichtlinie (WRRL), implementiert in nationales Recht:

- Wasserhaushaltsgesetz (WHG), Bayerisches Wassergesetz (BayWG)
- Grundwasserverordnung (GrwV), Oberflächengewässerverordnung (OGewV)
- EuGH-Urteil vom 01.07.2015, BVerwG-Urteil vom 11.08.2016 zum Begriff „Verschlechterung“ sowie weitere Gerichtsurteile

Rechtlicher Prüfrahmen

- **Räumliche Bezugsgröße** gem. § 6 WHG: Wasserkörper (OWK, GWK)
- **Bewirtschaftungsziele oberirdische Gewässer** (OWK) gem. § 27 WHG: Verschlechterungsverbot, Zielerreichungsgebot (getrennte Prüfung) für ökologischen Zustand/das ökologische Potenzial und den chemischen Zustand des OWK
- **Bewirtschaftungsziele Grundwasser** (GWK) gem. § 47 WHG: Verschlechterungsverbot, Zielerreichungsgebot für mengenmäßigen und chemischen Zustand, Gebot der Trendumkehr

FB EU-WRRL - Grundlagen

Rechtlicher Prüfrahmen

- **Ort der Beurteilung des Verschlechterungsverbots**:
  die repräsentative(n) Messstelle(n) für den GWK in seiner Gesamtheit, die repräsentative(n) operativen Messstellen für den FWK in seiner Gesamtheit;

  lokal begrenzte Veränderungen sind nicht relevant, solange sie sich nicht auf WK auswirken (BVerwG, Urteil 9.2.2017, Rn. 506)
  - gilt unabhängig von der konkreten Entfernung von der/den Messstellen
  - wenn mehrere Messpunkte/-strecken für 1 repräsentative Messstelle: ausschlaggebend ist Mittelwert
  - auch mögliche Wirkungen auf andere WK prüfen
- **Ausnahmen** von Verschlechterungsverbot und Zielerreichungsgebot: § 31 WHG

FB EU-WRRL - Grundlagen

Fachliche Vorgaben

- Umweltatlas Bayern – Gewässerbewirtschaftung
  >> IST-Zustand Wasserkörper, Messstellen/-strecken, Wasserkörpersteckbriefe…
  >> Geodaten mit Grenzen, Lage Messstellen liegen nicht vor
- Umsetzung WRRL - Bewirtschaftungsplan Donau 2022 bis 2027
  >> Bewirtschaftungsziele, Zielerreichung etc.
- Maßnahmenprogramm Donau 2022 bis 2027
  >> Maßnahmen zur Erreichung der Bewirtschaftungsziele, Gewässersteckbriefe
- Umsetzungskonzept Hydromorphologische Maßnahmen für den Flusswasserkörper „Donau von Einmündung Naab bis Einmündung Große Laber (FWK 1_F348) – Bundeswasserstraße (WWA Regensburg 2017).
  >> betrifft auch den PA 10

FB EU-WRRL - Grundlagen

Vollzugshinweise/-hilfen, Leitfäden

- Leitfaden zur Erstellung des Fachbeitrags Wasserrahmenrichtlinie (WRRL) bei Vorhaben der WSV an BWaStr (BMVI 2019)
- Handlungsempfehlung Verschlechterungsverbot (LAWA 2017)
  >> rechtliche Einordnung zum Verschlechterungsverbot, Prüfschemata für Grundwasserkörper
- Fachtechnische Hinweise für die Erstellung der Prognose i.R. des Vollzugs des Verschlechterungsverbots (LAWA 2020)
  >> Prüfvorgang für Oberflächenwasserkörper, Entscheidungshilfen
- Internetplattform Gewässerbewertung.de (gefördert durch UBA und LAWA)
  >> umfassende Bewertungshinweise, Leitfäden, Links…

Anmerkungen - Hinweise

FB EU-WRRL – Methodik

Ablaufschema zur Erarbeitung des Fachbeitrages WRRL

Nach LAWA 2020:

Vorstufe: Ermittlung Prüfbedarf

Stufe 1: Vorprüfung

Stufe 2: Detailprüfung

Prognose Auswirkungen

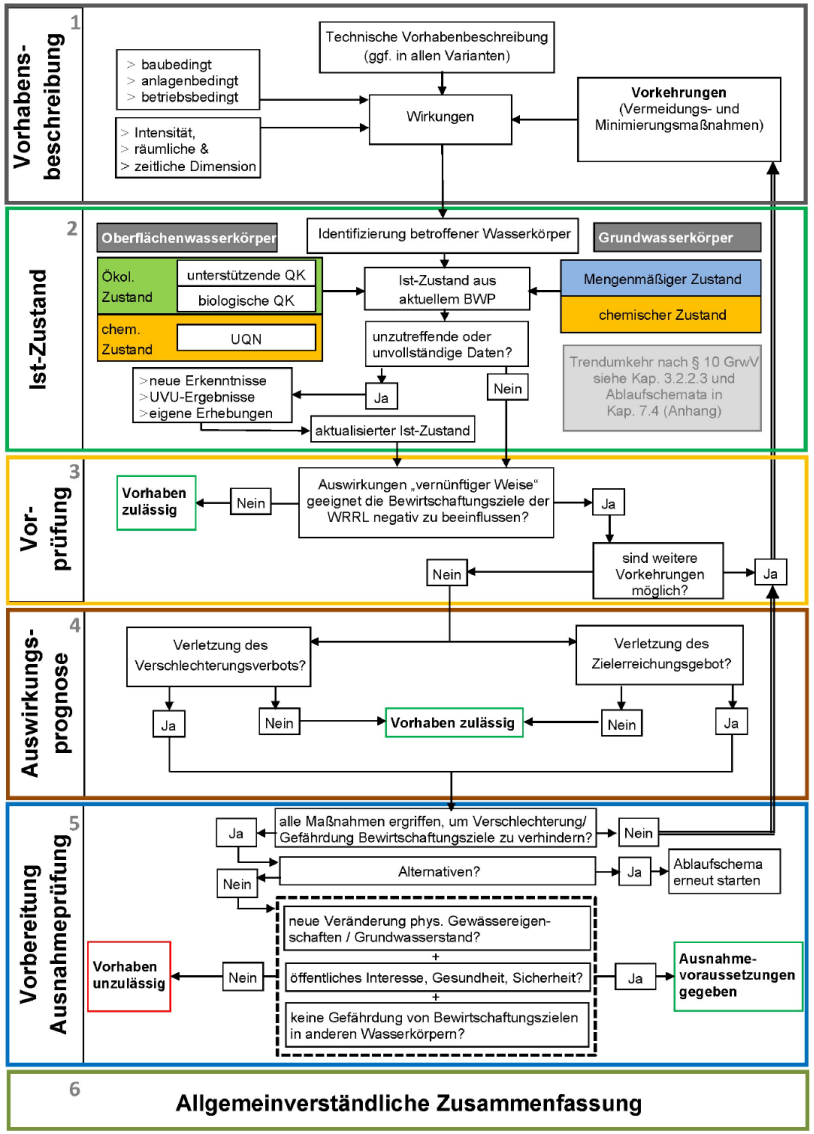

Quelle: BMVI 2019, S. 17

FB EU-WRRL - Grundlagen

Berichtsgliederung

1. Einleitung
2. Rechtliche und methodische Grundlagen
3. Beschreibung des Vorhabens und der damit verbundenen Wirkfaktoren, Ermittlung möglicher Vorkehrungen
4. Identifizierung und Beschreibung der betroffenen Wasserkörper
5. Vorprüfung

>> Wenn keine negativen Beeinflussung betroffener WK: Zusammenfassende Prognose

>> Wenn negative Beeinflussung Bewirtschaftungsziele: Detailprüfung Einzelaspekte

6. Beschreibung / Bewertung der zu erwartenden Auswirkungen
7. Prüfung auf Verstoß gegen das Verschlechterungsverbot
8. Prüfung auf Verstoß gegen das Zielerreichungsgebot
9. Vorbereitung der Ausnahmeprüfung
10. Zusammenfassende Prognose

IST-Zustand - Wasserkörper im Vorhabenbereich

Grundwasserkörper

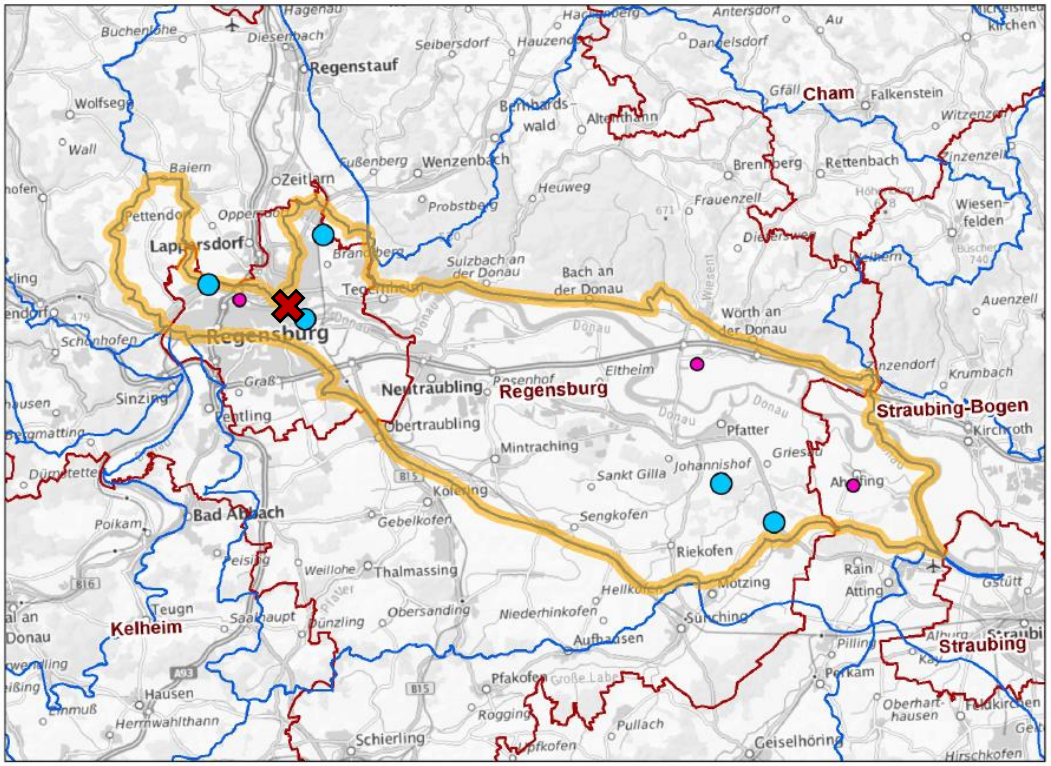

1_G083
Quartär - Regensburg

Abgrenzung des gewählten Grundwasserkörpers

Messnetz zur Zustandsbeurteilung des ausgewählten Grundwasserkörpers

- Messstelle Zustand Chemie
- Messstelle Zustand Menge

Grundwasserkörper
Landkreise

0 4,5 9 Kilometer

Fachdaten: Informationssystem Wasserwirtschaft: © Bayerisches Landesamt für Umwelt

Geobasisdaten:
Verwaltungsgrenzen250: © Bayerische Vermessungsverwaltung, 2019
WMTSTopPlusOpen Graustufen (Upscale): © Bundesamt für Kartographie und Geodäsie, 2021
Dezember 2021

✖ Ungefähre Lage HWS-H Maßnahme

Quelle: Steckbrief Grundwasserkörper Bewirtschaftungszeitraum 2022-2027 (Umweltatlas, LfU 21.12.2021, online; ergänzt)

IST-Zustand - Wasserkörper im Vorhabenbereich

IST-Zustand Grundwasserkörper 1_G083

Zustand Chemie	2015	Aktuell
Zustand (gesamt)	Schlecht	Schlecht

Komponenten		
Nitrat	Üa	Üa
Pflanzenschutzmittel - Wirkstoffe und relevante Metaboliten	KÜ	KÜ
Pflanzenschutzmittel - nicht relevante Metaboliten	Nk	Üa
Anlage 2 - Sonstige Stoffe		
Ammonium	KÜ	KÜ
Ortho-Phosphat	KÜ	KÜ
Nitrit	KÜ	KÜ
Sulfat	KÜ	KÜ
Chlorid	KÜ	KÜ
Arsen	KÜ	KÜ
Cadmium	KÜ	KÜ
Blei	KÜ	KÜ
Quecksilber	KÜ	KÜ
Tri- und Tetrachlorethen	KÜ	KÜ

Weitere relevante Stoffe (wegen GVAÖ)
-

Zustand Menge	2015	Aktuell
Zustand	Gut	Gut

Grundwasserbilanzierung	2015	Aktuell
Anteil Entnahme an der Grundwasserneubildung [%]	2,9	7,8

Legende - Code	Beschreibung
Gut	Zustand gut
Schlecht	Zustand schlecht
Nk	Nicht klassifiziert
KÜ	Keine Überschreitung Schwellenwert
Üa	Überschreitung Schwellenwert anthropogen bedingt
ÜK	Überschreitung Schwellenwert Klärungserfordernis
Üg	Überschreitung Schwellenwert geogen bedingt

Abkürzungen	Bedeutung
ATKIS	Amtliches Topographisch-Kartographisches Informationssystem
GWK	Grundwasserkörper
GVAÖ	Grundwasserverbundene aquatische Ökosysteme
LAWA	Bund/Länder-Arbeitsgemeinschaft Wasser
WHG	Wasserhaushaltsgesetz
N	Natürliche Gegebenheiten
T	Technische Durchführbarkeit
U	Unverhältnismäßig hoher Aufwand

Zielerreichung/Ausnahmen	Chemie	Menge
Bewirtschaftungsziel erreicht	Nein	Ja
Prognostizierter Zeitpunkt der Zielerreichung	2028 - 2033	-
Fristverlängerung (§ 29 WHG)	Ja	-
Begründung(en) für Fristverlängerung bzw. abweichende Bewirtschaftungsziele	N	-

Ergänzende Maßnahmen - Maßnahmenbezeichnung gemäß LAWA-Maßnahmenkatalog	LAWA-CODE	Umfang bis 2027	Umfang nach 2027
-	-	-	-

Grundwasserabhängige Landökosysteme: aktuell keine nachteilige Beurteilung des GWK, da gute GW-Menge

Quelle: Steckbrief Grundwasserkörper Bewirtschaftungszeitraum 2022-2027 (Umweltatlas, LfU 21.12.2021, online)

Maßnahmen Landwirtschaft: AVDüV 01.01.2021

IST-Zustand - Wasserkörper im Vorhabenbereich

Flusswasserkörper

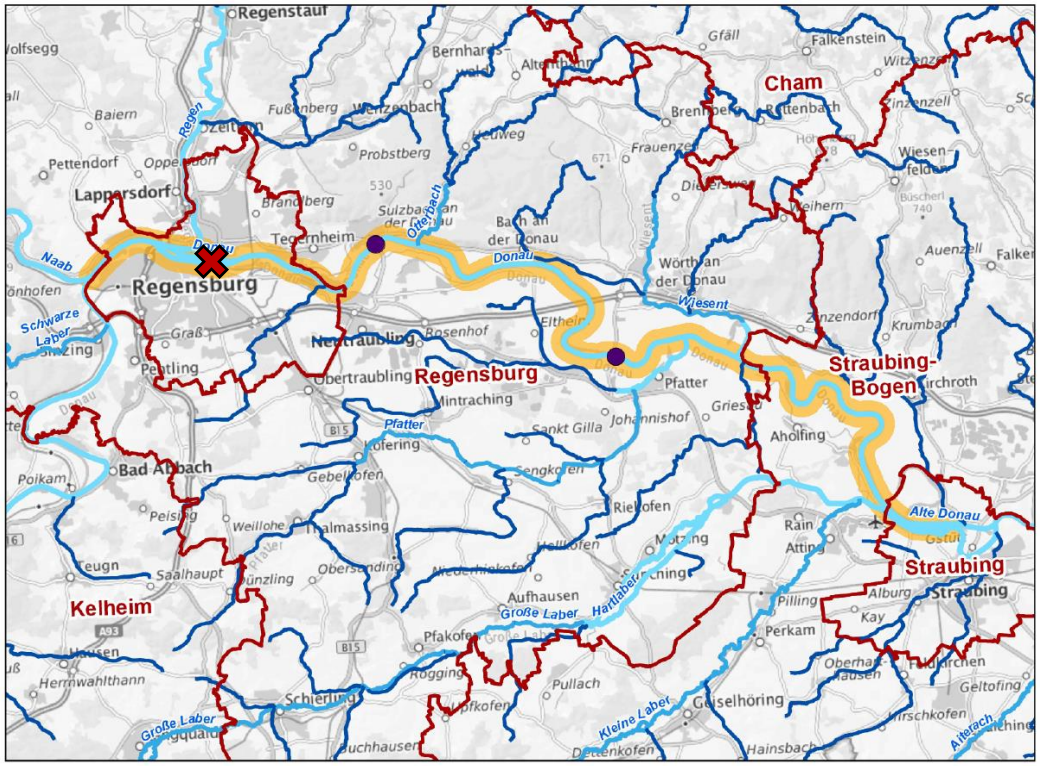

1_F348

Donau von Einmündung Naab bis Einmündung Große Laber

Abgrenzung des gewählten Flusswasserkörpers

Messnetz zur Zustandsbewertung des ausgewählten Flusswasserkörpers

Operative Messstelle

Seen

Gewässer 1. Ordnung

Gewässer 2. Ordnung

Gewässer 3. Ordnung

Nicht zuordenbar

Landkreise

0 4 8 Kilometer

Fachdaten: Informationssystem Wasserwirtschaft: © Bayerisches Landesamt für Umwelt

Geobasisdaten: Verwaltungsgrenzen25: © Bayerische Vermessungsverwaltung, 2021
WMTSTopPlusOpen Graustufen (Upscale): © Bundesamt für Kartographie und Geodäsie, 2021
Dezember 2021

Ungefähre Lage HWS-H Maßnahme

Quelle: Steckbrief Oberflächenwasserkörper Bewirtschaftungszeitraum 2022-2027 (Umweltatlas, LfU 21.12.2021, online; ergänzt)

IST-Zustand - Wasserkörper im Vorhabenbereich

IST-Zustand Flusswasserkörper 1_F348

Ökologischer Zustand	2015	Aktuell
Zustand (Z)/Potenzial (P) (gesamt)	P3	P3

Chemischer Zustand	2015	Aktuell
Zustand (gesamt)	Nicht gut	Nicht gut

Biologische Qualitätskomponenten	2015	Aktuell
Phytoplankton	3	2
Makrophyten/Phytobenthos	3	3
Makrozoobenthos	3	3
Fischfauna	3	3

Differenzierte Angaben zum chemischen Zustand	2015	Aktuell
- ohne ubiquitäre Schadstoffe*	Gut	Gut
- ohne Quecksilber und BDE	Nk	Gut

* Die Bewertungen sind wegen Änderungen der Vorgaben nicht direkt vergleichbar

Unterstützende Qualitätskomponenten	2015	Aktuell
Hydromorphologie		
Wasserhaushalt	Nbr	H3
Durchgängigkeit	Nbr	H3
Morphologie	Nbr	H3
Physikalisch-chemische Qualitätskomponenten		
Temperaturverhältnisse	Nbr	Ne
Sauerstoffhaushalt	Nbr	E
Salzgehalt	Nbr	E
Versauerungszustand	Nk	E
Nährstoffverhältnisse	Ne	E

Prioritäre Stoffe mit Überschreitung der Umweltqualitätsnormen (UQN)
Quecksilber
Summe 6-BDE (28,47,99,100,153,154)

Legende - Code	Beschreibung
1 / Z1	Ökologischer Zustand sehr gut
2 / Z2 / P2	Ökologischer Zustand gut/ökologisches Potenzial gut und besser
3 / Z3 / P3	Ökologischer Zustand/ökologisches Potenzial mäßig
4 / Z4 / P4	Ökologischer Zustand/ökologisches Potenzial unbefriedigend
5 / Z5 / P5	Ökologischer Zustand/ökologisches Potenzial schlecht
Nk	Nicht klassifiziert
E	Wert eingehalten
H1 / H2	Gut oder besser
Ne	Wert nicht eingehalten
H3	Schlechter als gut
Nbr	Untersuchung durchgeführt, nicht bewertungsrelevant
Gut	Chemischer Zustand gut
Nicht gut	Chemischer Zustand nicht gut

- Gewässertyp 10: Kiesgeprägte Ströme
- Erheblich veränderter Wasserkörper (§ 28 WHG)

Quelle: Steckbrief Oberflächenwasserkörper (Umweltatlas, LfU 21.12.2021, online)

IST-Zustand - Wasserkörper im Vorhabenbereich

IST-Zustand Flusswasserkörper 1_F348

Zielerreichung/Ausnahmen	Ökologie	Chemie
Bewirtschaftungsziel erreicht	Nein	Nein
Prognostizierter Zeitpunkt der Zielerreichung	Nach 2045	Nach 2045
Fristverlängerung (§ 29 WHG)	Ja	Ja
Begründung(en) für Fristverlängerung bzw. abweichende Bewirtschaftungsziele	T	N

- Umfangreiches Maßnahmenprogramm
- WWA 2017: Umsetzungskonzept Maßnahmenprogramm für FWK 1_F348

>> Projekt-Maßnahmen zur naturnahen Auen- und Uferumgestaltung PA 10 setzen Teile des Maßnahmenprogramms um

Ergänzende Maßnahmen - Maßnahmenbezeichnung gemäß LAWA-Maßnahmenkatalog**	LAWA-CODE	Synergien mit anderen Richtlinien	Umfang bis 2027	Umfang nach 2027
Optimierung der Betriebsweise kommunaler Kläranlagen	5	-	1 Anlage(n)	-
Maßnahmen zur Reduzierung der Nährstoffeinträge durch Anlage von Gewässerschutzstreifen	28	Natura 2000	-	-
Maßnahmen zur Gewährleistung des erforderlichen Mindestabflusses	61	Natura 2000	6 Maßnahme(n)	-
Maßnahmen zur Förderung des natürlichen Wasserrückhalts	65	Natura 2000	10 km²	-
Maßnahmen zur Herstellung/Verbesserung der linearen Durchgängigkeit an Staustufen/Flusssperren, Abstürzen, Durchlässen und sonstigen wasserbaulichen Anlagen gemäß DIN 4048 bzw. 19700 Teil 13	69	Natura 2000	1 Maßnahme(n)	2 Maßnahme(n)
Maßnahmen zur Habitatverbesserung durch Initiieren/Zulassen einer eigendynamischen Gewässerentwicklung	70	Natura 2000	20 km	-
Maßnahmen zur Habitatverbesserung im vorhandenen Profil	71	Natura 2000	20 km	-
Maßnahmen zur Habitatverbesserung im Gewässer durch Laufveränderung, Ufer- oder Sohlgestaltung	72	Natura 2000	10 km	-
Maßnahmen zur Habitatverbesserung im Uferbereich	73	Natura 2000	20 km	-
Maßnahmen zur Auenentwicklung und zur Verbesserung von Habitaten	74	Natura 2000	10 km²	-
Anschluss von Seitengewässern, Altarmen (Quervernetzung)	75	Natura 2000	10 Maßnahme(n)	-
Technische und betriebliche Maßnahmen vorrangig zum Fischschutz an wasserbaulichen Anlagen	76	-	3 Maßnahme(n)	-
Maßnahmen zur Verbesserung des Geschiebehaushaltes bzw. Sedimentmanagement	77	-	3 Maßnahme(n)	-
Maßnahmen zur Reduzierung der Belastungen infolge Bauwerke für die Schifffahrt, Häfen, Werften, Marinas	81	-	20 Maßnahme(n)	-
Maßnahmen zur Reduzierung anderer hydromorphologischer Belastungen	85	Natura 2000	5 Maßnahme(n)	-
Maßnahmen zur Eindämmung eingeschleppter Spezies	94	-	1 Maßnahme(n)	-
Vertiefende Untersuchungen und Kontrollen	508	-	1 Maßnahme(n)	-

** Nicht einzeln aufgelistet werden Maßnahmen gegen die diffusen Quellen, die zu einer flächendeckenden Belastung mit den ubiquitären Schadstoffen Quecksilber und Bromierte Diphenylether (BDE) führen.

Quelle: Steckbrief Oberflächenwasserkörper (Umweltatlas, LfU 21.12.2021, online)

FB EU-WRRL - Vorgehen

Prüfschema Grundwasserkörper

Quelle: LAWA 2017, ergänzt

Mengenmäßiger Zustand GWK

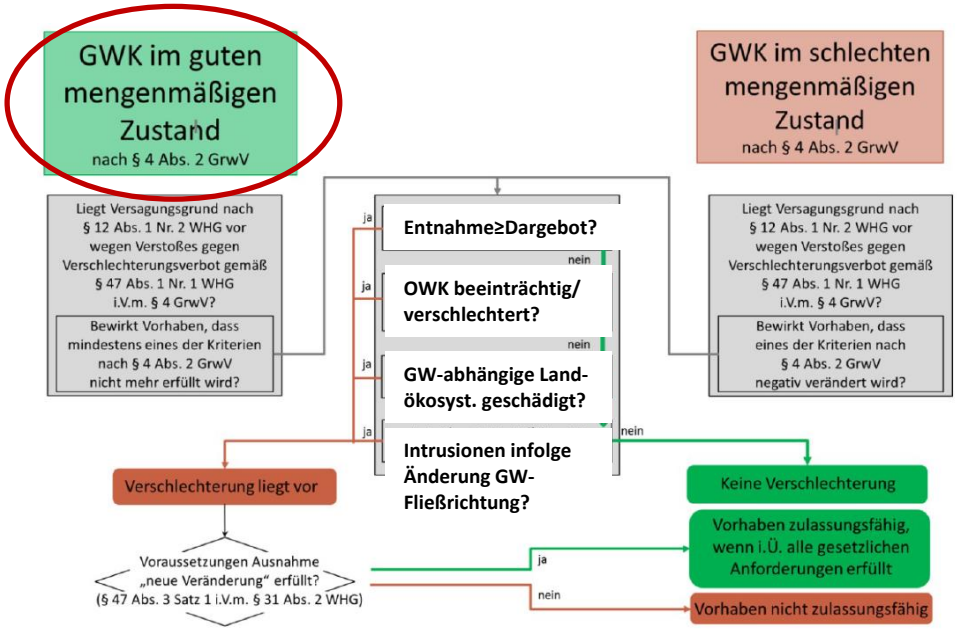

Chemischer Zustand GWK

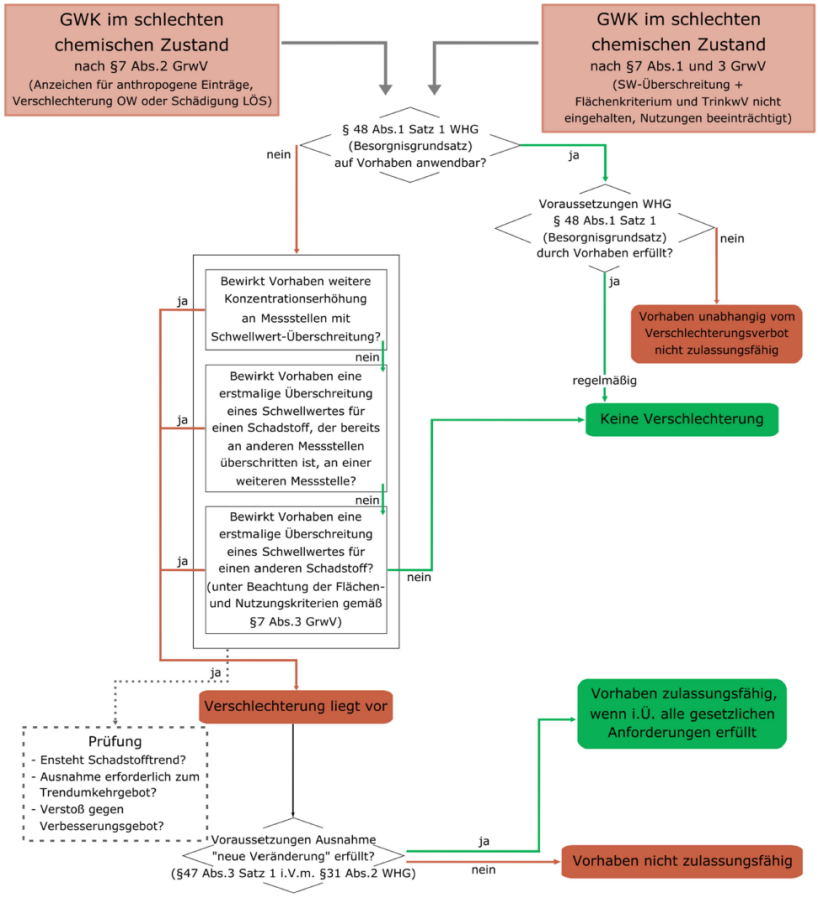

FB EU-WRRL - Vorgehen

Prüfschema Oberflächenwasserkörper (LAWA 2020)

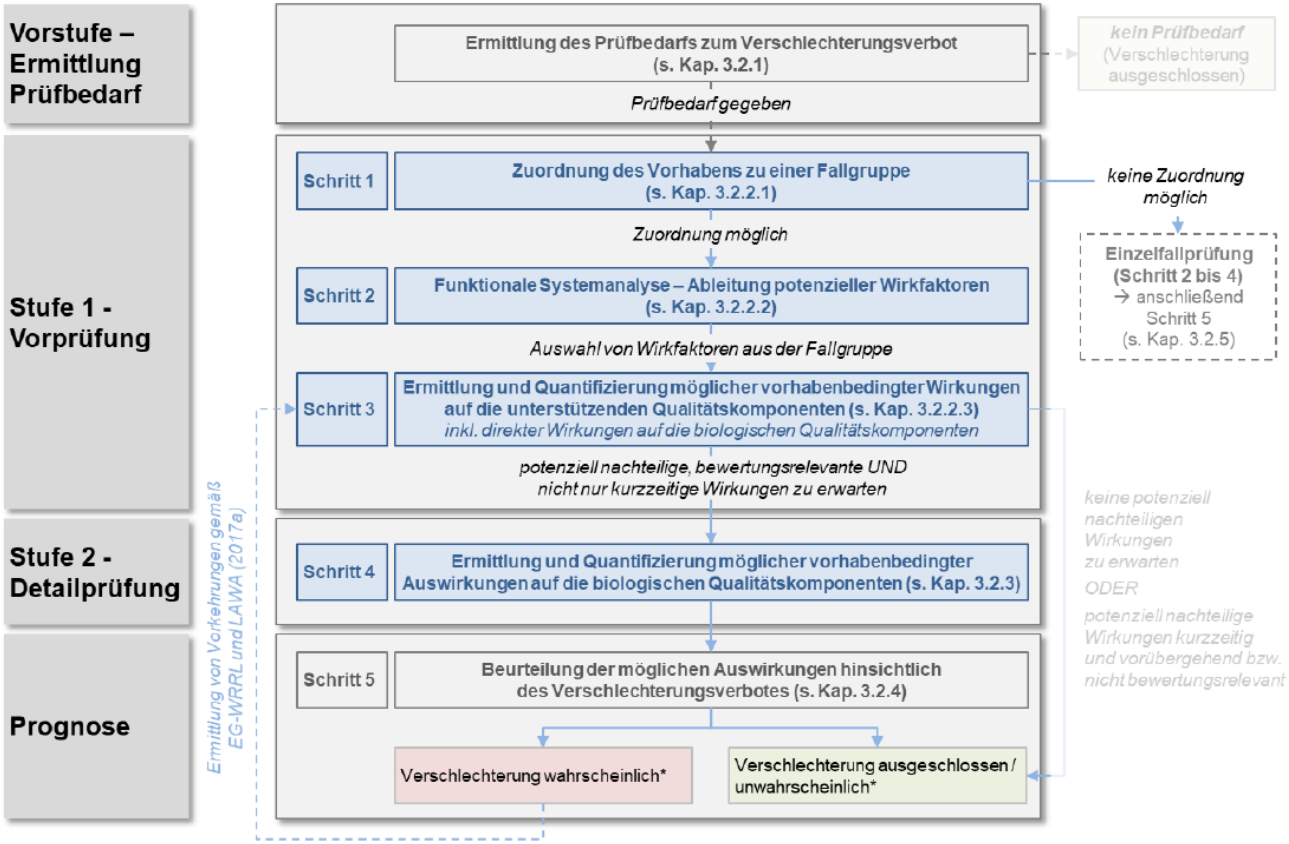

* „hinreichende" Wahrscheinlichkeit des möglichen Schadenseintritts nach aktueller deutscher Rechtsprechung (BVerwG 2017)

FB EU-WRRL - Zusammenfassung

- **Der Bezugsraum der Prognose ist der Wasserkörper, Ort der Beurteilung sind die Messstellen für den GWK bzw. die operativen Messstellen für den FWK**
  >> lokale Eingriffe in einen Wasserkörper, die nicht mit größeren Ein- oder Ausleitungen, Querbauwerken oder sonstigen umfangreichen Gewässerausbauvorhaben in Verbindung stehen, haben im Vergleich zur Eingriffsregelung (BNatSchG) und der UVP-Vorprüfung (UVPG) dadurch i.d.R. eine geringere Relevanz.
- **Ersteinschätzung:** das Vorhaben wird die Erheblichkeitsschwelle bezüglich der Beeinträchtigung der Bewirtschaftungsziele nach EU-WRRL wahrscheinlich nicht überschreiten. Für den FWK 1_F348 wird das Vorhaben eine Verbesserung erzielen. Eine finale Einschätzung ist nach Vorlage der Ergebnisse der Grundwasser-Modellierung und der Hydraulischen Modellierung möglich.

FB EU-WRRL - Diskussion

Hinweise – Fragen – Anmerkungen

- Weitere Grundlageninformationen, Vollzugshinweise, Geodaten
- Weitere Hinweise

Vielen Dank!