14 125 HWS Regensburg Abschnitt H

Übersicht Tore und Durchfahrten

Hinweis: HWS-Höhen noch auf Stand ohne Angaben aus Hydraulik BCE vom 21/10/2019 !

Die Ergebnisse aus den Festlegungen beim JF31 am 25.11.2019 sind direkt in grüner Schrift bei den einzelnen Toren vermerkt !

Nr.	PA	Lage, Bezeichnung	ca. Abmessungen	Erläuterung	Ausschnittskizze	Anmerkungen Team 3
1a	1	Durchfahrt zw. Haus 53 und 55	B = 2,50m; H = 2,25 m	Tor oder DB-System?		Nähe Punkt 80
						Schadenspotential hoch
						Klasse I, 1,5 m < h < 3m
		Durchfahrt zurückversetzt				redundant ausbilden
		geringes Anprallpotential				oder Rückabstützung?
		schnell ansteigendes Gelände				Privatbesitz!
		hinter dem Durchgang				
		Tore wartungsintensiver als DB				zusätzlich FB-Bereich Veranda
						schließen (b=1,70, h=0,35)
		Durchfahrt mit DB ausbilden!				Sandsäcke?
		keine Redundanz erforderlich!				
		2. Schutzlinie mittels Sandsäcken				
1b	1	Treppenaufgang Haus 53	B = 1,15m; H = 0,48 m	DB-System		Nähe Punkt 79
						Schadenspotential gering
						Klasse III, h < 1,5m
						nicht redundant ausbilden
		keine Redundanz erforderlich!				
		Sandsäcke vorhalten				Privatbesitz!

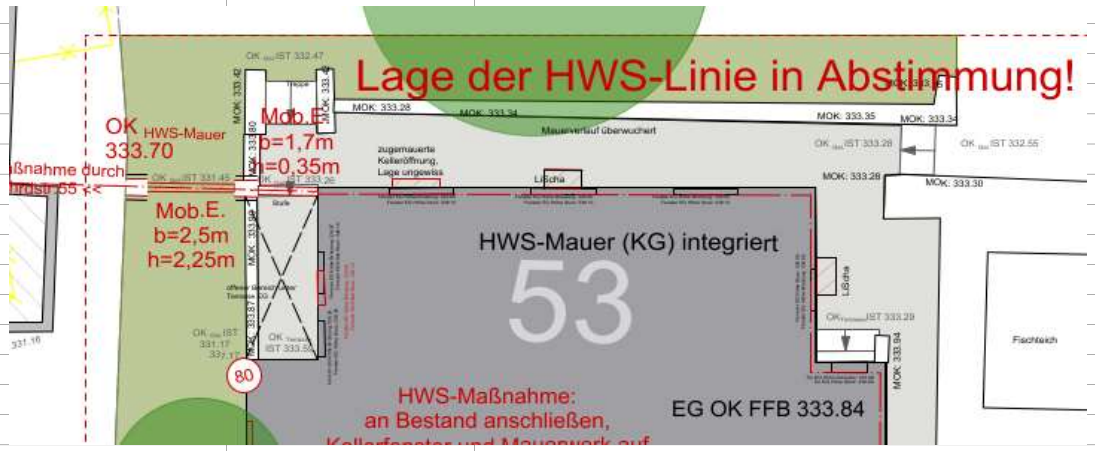

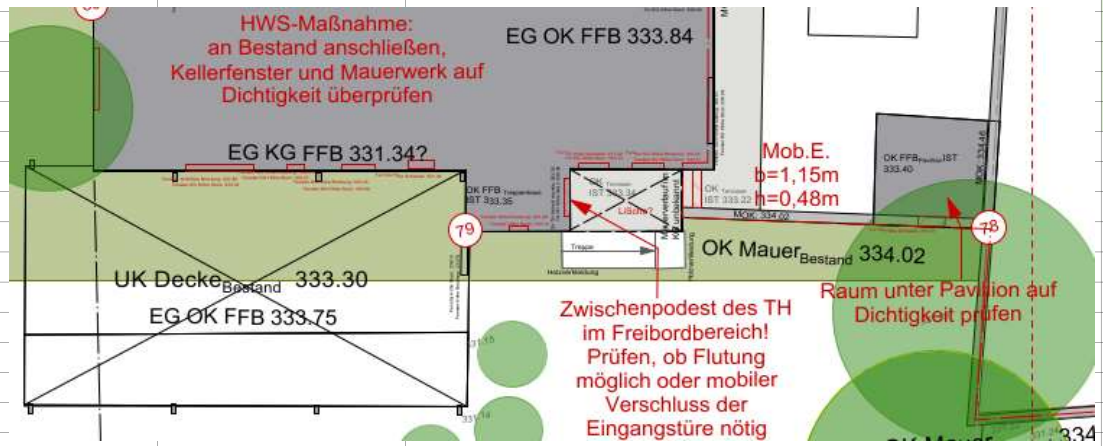

2	1	Tor Obstbaumwiese Haus 41	B = 1,50m; H = 0,70 m	Tor oder DB-System?		Punkt 72, Schnitt 1.6
						Schadenspotential gering
						Klasse III, h < 1m
		Durchgang mit DB ausbilden!				nicht redundant ausbilden
		keine Redundanz erforderlich!				
		Sandsäcke vorhalten				
		Lage noch optimieren				
3	1	Tor Obstbaumwiese Haus 41	B = 1,50m; H = 0,70 m	Tor oder DB-System?	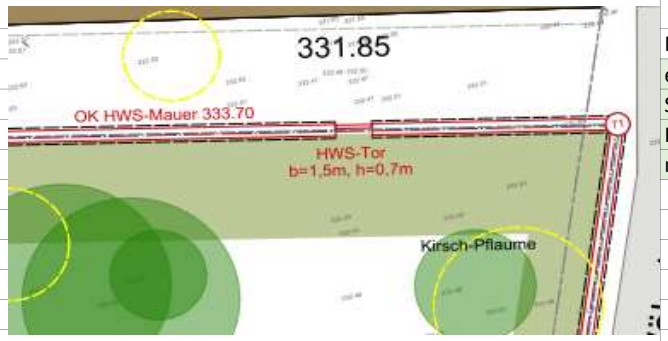	Nähe Punkt 71
						entfällt vermutlich
						Schadenspotential gering
						Klasse III, h < 1m
		entfällt, siehe Nr. 2				nicht redundant ausbilden
4	1	Durchgang Wöhrdstraße Haus 37f	B = 5,0m; H = 1,70 m	DB-System	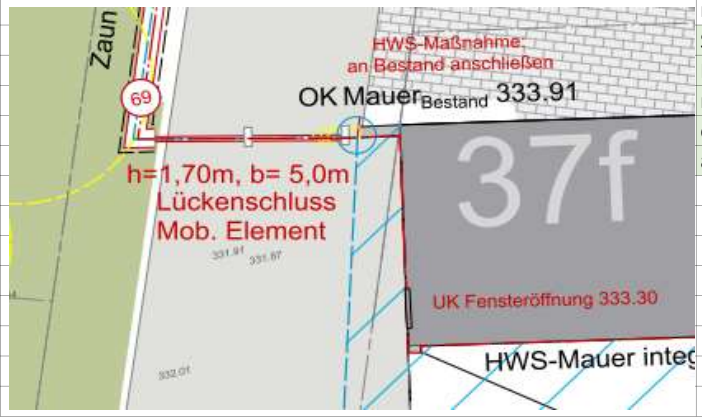	rechts neben Punkt 69
						Schadenspotential hoch
						Klasse I, 1,5 m < h < 3m
						redundant ausbilden
		Durchfahrt mit DB ausbilden!				oder Rückabstützung?
		redundant ausbilden!				alternativ Tor?
		zweite Schutzlinie muss nicht zwingend gleich mit aufgabut werden				

5	1	Tor Haus 33b (Privat)	B = 1,3m; H = 1,58m	Tor Bestand	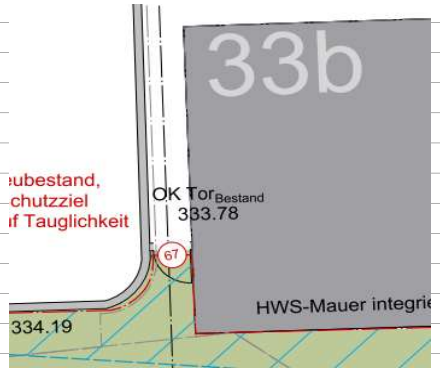	Punkt 67
						OK = 333,78 mNN
						erf OK = 333,74 mNN
		keine Redundanz erforderlich!				Schadenspotential gering ?
		Sandsäcke vorhalten				Klasse III, h > 1,5 m
		Nachweis erforderlich				redundant ausbilden?
						Privatbesitz
6	1	Tor Haus 33a (Privat)	B = 1,3m; H = 1,64m	Tor Bestand	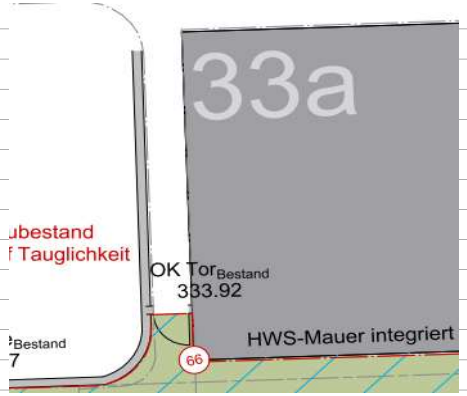	Punkt 66
						OK = 333,92 mNN
						erf OK = 333,74 mNN
		keine Redundanz erforderlich!				Schadenspotential gering ?
		Sandsäcke vorhalten				Klasse III, h > 1,5 m
		Nachweis erforderlich				redundant ausbilden?
						Privatbesitz
7	1	Durchgang Straße Haus 31c	B = 5,0m; H = 1,35 m	DB-System	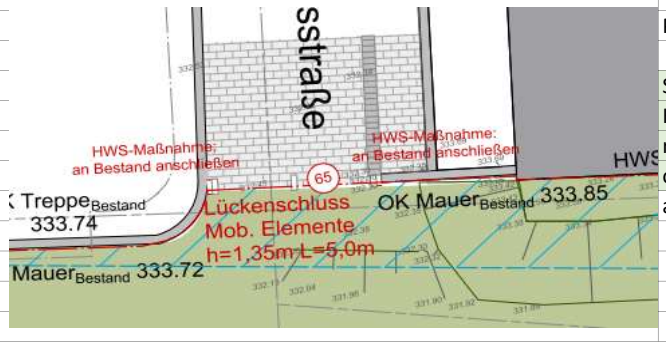	Punkt 65
						Schadenspotential hoch
						Klasse I, h < 1,5 m
		Durchfahrt mit DB ausbilden!				redundant ausbilden
		redundant ausbilden!				oder Rückabstützung?
		zweite Schutzlinie muss nicht zwingend gleich mit aufgabut werden				alternativ Tor?

8	2	Durchgang Maffeistraße	B = 3,5m; H = 1,40 m	Tor 1-flügelig außen	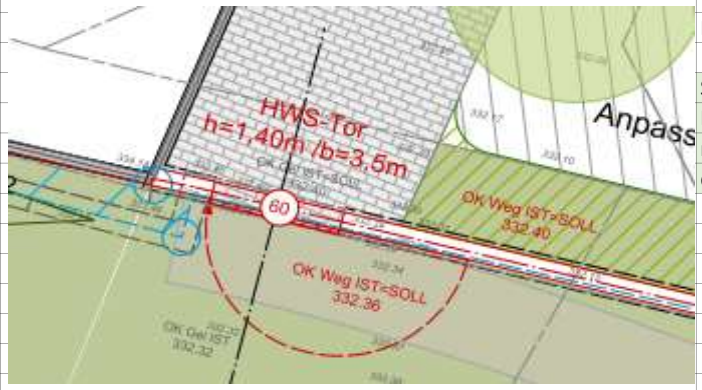	Punkt 60, Schnitt 2.1
						Schadenspotential hoch
		kein Tor wegen Wartung				Klasse I, h < 1,5 m
		Durchfahrt mit DB (2 x 2,50m) ausbilden!				nicht redundant ausbilden
		redundant ausbilden!				da Tor ?
		zweite Schutzlinie muss nicht zwingend gleich mit aufgabut werden				
9	3	Durchgang Deich	B = 2,90m; H = 1,10 m	Tor 2-flügelig?	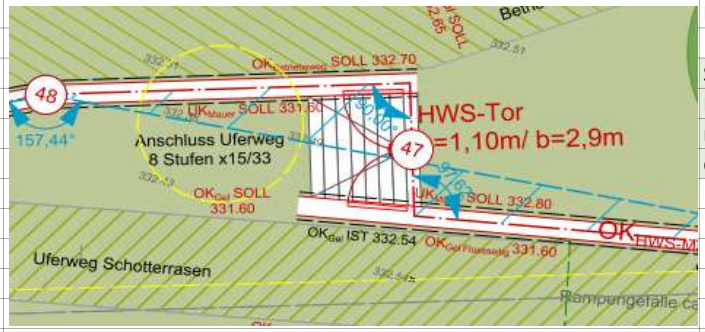	Punkt 47
						Schadenspotential gering
		liegt im Strömungsschatten				Klasse III, h < 1,5 m
		keine Redundanz erforderlich!				nicht redundant ausbilden
		Durchgang mit DB ohne Mittelstütze ausbilden!				da Tor ?
		Sandsäcke vorhalten				
10	3	Durchgang Deich	B = 5,00m; H = 0,60 m	DB-System	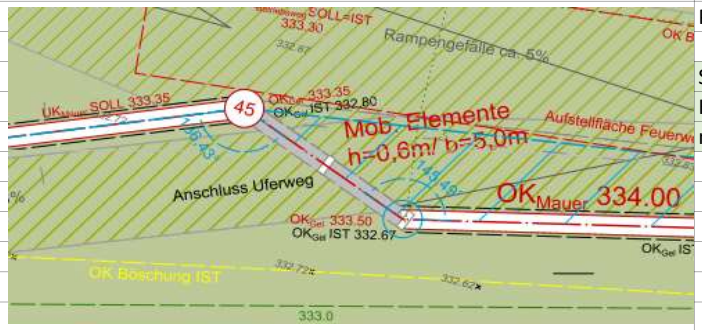	Punkt 45
						Schadenspotential gering
		liegt im Strömungsschatten				Klasse III, h < 1m
		keine Redundanz erforderlich!				nicht redundant ausbilden
		Durchgang mit DB ausbilden!				
		Sandsäcke vorhalten				

11	3	Tor Deich Westspitze	B = 5,75m; H = 1,15 m	Schiebetor mechanisch	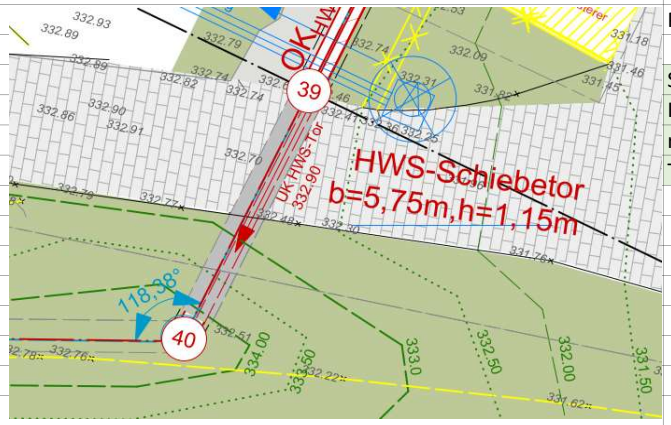	Punkt 39, Schnitt 3.5
						Schadenspotential hoch
						Klasse I, 1,5 m < h < 3m
		hohes Anprallpotential				redundant ausbilden
		mobile Treibgutabweiser vorsehen?				Treibgutabweiser vorsehen?
		Ausbildung als Schiebetor wegen Schräganschluss Deich				
		Redundanz erforderlich!				
		2. Schutzlinie mittels DB				
		Alternative mit Variante Flügelmauer prüfen				
12	5	Tor Wöhrdstraße Haus 10	B = 0,90 m; H = 1,70 m	Tor 1-flügelig	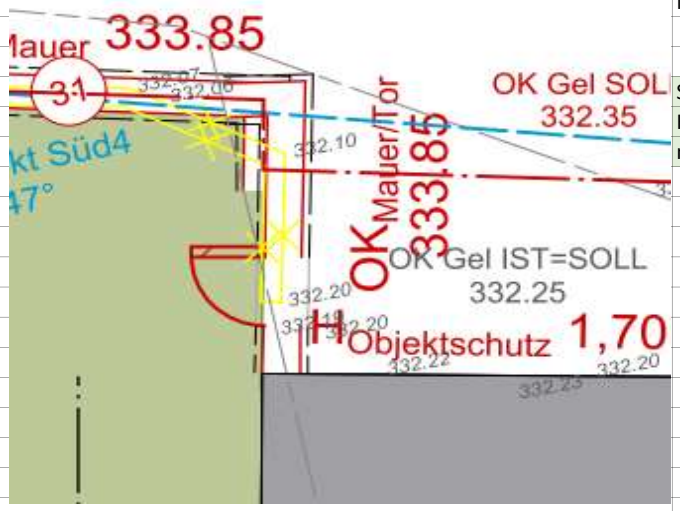	Nähe Punkt 31
						Schadenspotential gering
		liegt im Strömungsschatten				Klasse III, 1,5 m < h < 3m
		keine Redundanz erforderlich!				nicht redundant ausbilden
		Durchgang mit DB ausbilden! kein Tor				
		Sandsäcke vorhalten				

13	5	Garage Wöhrdstraße Haus 10	B = 5,00m; H = 1,70 m	DB-System	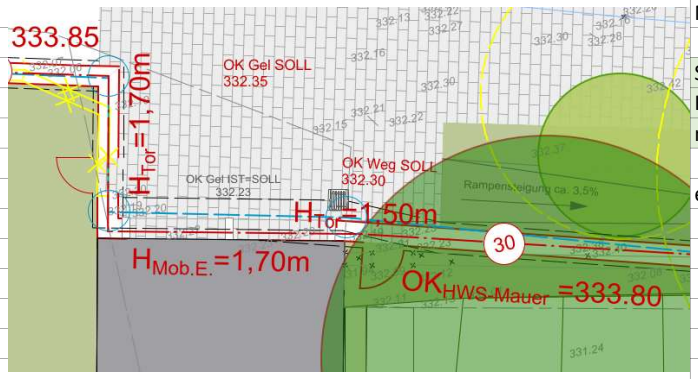	Nähe Punkt 30
						Schadenspotential gering
		liegt im Strömungsschatten, liegt im Baumfallbereich				Klasse III, 1,5 m < h < 3m
		keine Redundanz erforderlich!				nicht redundant ausbilden
		Einfahrt mit DB ausbilden!				
		Sandsäcke vorhalten				event. In Kombination mit Nr. 14?
		keine Gefährdung durch Baumfall, abgedeckt durch Baukörper				
14	5	WSA Zugang Mühlkanal	B ca. 1,0 m; H = 1,50 m	Tor 1-flügelig	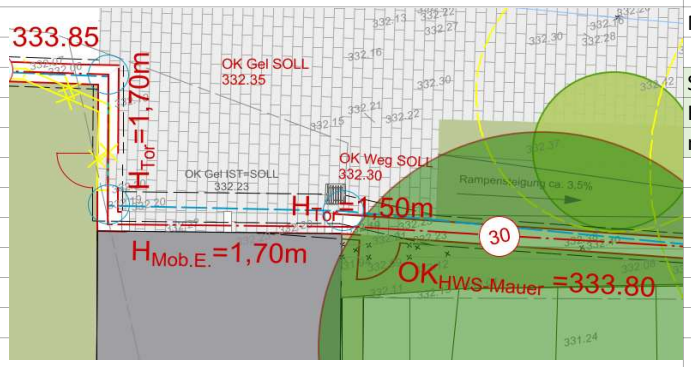	Nähe Punkt 30
			in Kombination mit Nr. 13			
			B = 10,0 m; H = 1,50 m			Schadenspotential gering
						Klasse III, 1,5 m < h < 3m
		liegt im Strömungsschatten, liegt im Baumfallbereich				nicht redundant ausbilden
		keine Redundanz erforderlich!				
		Durchgang WSA als Tor ausbilden!				
		Sandsäcke vorhalten				
		Gefährdung durch Baumfall, Schutz vorsehen (Torbogen, Rahmen etc.)				
		rechnerischer Nachweis erforderlich				
		Präferenz: Zugang kann entfallen				
15	5	Öffnung Wiese	B = 7*2,5 m; H = 1,10 m	DB-System		zwischen Punkt 28 und 29
		liegt im Strömungsschatten, Bäume in Böschung dienen als Abweiser				
		keine Baumpflanzungen in diesem Bereich vorsehen				Schadenspotential hoch
		keine Redundanz erforderlich!				Klasse I, h < 1,5m
		Öffnung mit DB ausbilden!				redundant ausbilden?
		Sandsäcke vorhalten, mit LKW anfahrbar				oder Rückabstützung?

16	5	Durchgang RÜB 19	B = 2,80 m	HW 100 frei	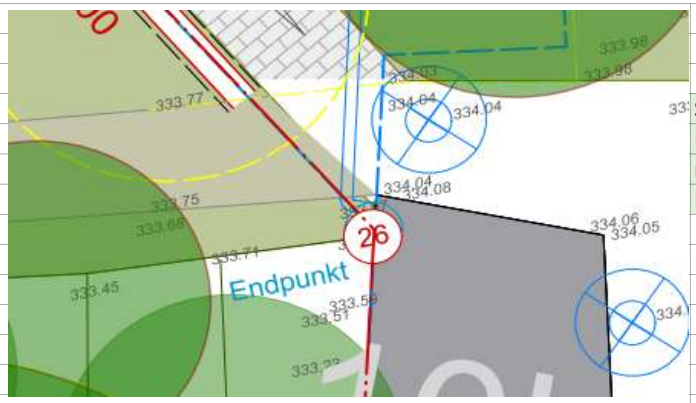	
			OK Gel = 333.90 m ü.NN	keine Maßnahme erford?		
						Schadenspotential gering
		keine Aktion erforderlich				Klasse III, h < 1,5m
		da Höhe > HW100 + FB				nicht redundant ausbilden
						Hw100-sicher
17	5	Treppe/Durchgang RÜB 19	B = 2,80 m	HW 100 frei	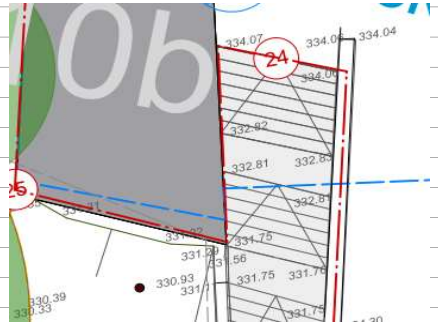	Punkt 24
			OK Gel = 334.06 m ü.NN	keine Maßnahme erford?		
						Schadenspotential gering
		keine Aktion erforderlich				
		da Höhe > HW100 + FB				Hw100-sicher
18	7	Durchfahrt Wöhrdtsr. Flaschenhals	B = 7,5 m; H = 2,40 m	DB-System	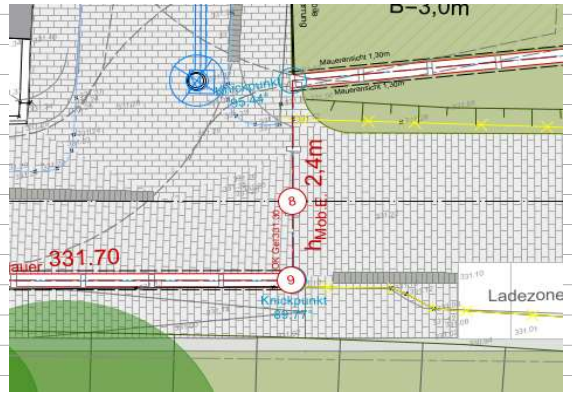	Punkt 8 Schnitt 7.3
		Ist nicht als Durchfahrt zu verstehen				Schadenspotential hoch
		ist linienförmige Fortsetzung der HWS-Wand				Klasse I, 1,5 m < h < 3 m
		keine Redundanz erforderlich!				redundant ausbilden
		Sandsäcke vorhalten				oder Rückabstützung?
		2. Schutzlinie nicht vermittelbar				

19	7	Durchfahrt Werftsr. Haus 27/28	B = 7,5 m; H = 2,20 m	DB-System		Punkt 6 Schnitt 7.4
						Schadenspotential hoch
						Klasse I, 1,5 m < h < 3 m
		ist linienförmige Fortsetzung der HWS-Wand				redundant ausbilden
		keine Redundanz erforderlich!				
		Sandsäcke vorhalten				
		2. Schutzlinie nicht vermittelbar und schränkt Betriebsweg ein				ev. Rückabstützung?
						(kollidiert mit Behelfsweg)
20	7	Durchfahrt Werftsr. Haus 28/29	B = 5,0 m; H = 2,20 m	DB-System	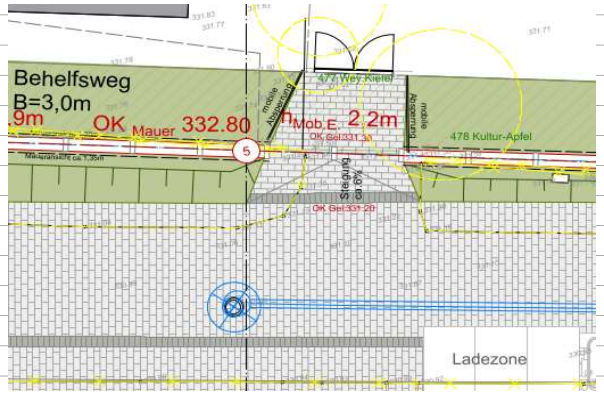	Punkt 5 Schnitt 7.5
						Schadenspotential hoch
		ist linienförmige Fortsetzung der HWS-Wand				Klasse I, 1,5 m < h < 3 m
		keine Redundanz erforderlich!				redundant ausbilden
		Sandsäcke vorhalten				
		2. Schutzlinie nicht vermittelbar und schränkt Betriebsweg ein				ev. Rückabstützung?
						(kollidiert mit Behelfsweg)
21	7	Durchfahrt Am Winterhafen	B = 7,5m; H = 2,0 m	DB-System	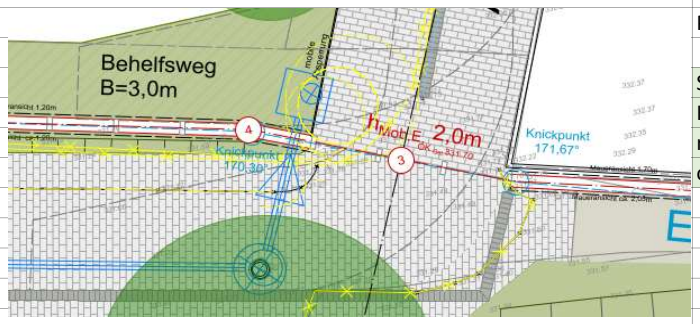	Punkt 3 Schnitt 7.6
		ist linienförmige Fortsetzung der HWS-Wand				Schadenspotential hoch
		keine Redundanz erforderlich!				Klasse I, 1,5 m < h < 3 m
		Sandsäcke vorhalten				redundant ausbilden
		2. Schutzlinie nicht vermittelbar und schränkt Betriebsweg ein				oder Rückabstützung?

Auszug DIN 19712 Ausgabe 2013-01

4.4 Klassifizierung

Im Hinblick auf eine Berücksichtigung unterschiedlicher Schadenspotenziale im zu schützenden Polderraum und zur Berücksichtigung der Größe einer Anlage sind Hochwasserschutzanlagen an Fließgewässern — in Anlehnung an Reihe DIN 19700 — in verschiedene Bauwerksklassen zu gruppieren. Tabelle 1 gibt eine Orientierungshilfe für die zu stellenden Anforderungen.

Tabelle 1 — Klassifizierung von Hochwasserschutzanlagen nach Bauwerkshöhe und Schadenspotenzial

Bauwerkshöhe h_{BW} m	Schadenspotenzial nach Tabelle 2		
	Hoch	Mittel	Gering
≥ 3	Klasse I	Klasse II	Klasse II
$3 > h_{BW} \geq 1{,}5$	Klasse I	Klasse II	Klasse III
$1{,}5 > h_{BW}$	Klasse I	Klasse III	Klasse III

ANMERKUNG Bei Deichen sollte im Falle langer Einstaudauer und/oder bei Böschungsneigungen 1 : m = 1 : 2 und steiler eine höhere Einstufung erfolgen. Bei kurzer Einstaudauer und/oder flacher Böschungsneigung (m > 3) kann eine niedrigere Einstufung erfolgen. Bei der Klassifizierung sollten die örtlichen Gegebenheiten und Erfahrungen sowie der spezifische Deichaufbau und –zustand beachtet werden.

Tabelle 2 — Objektkategorien und mögliche Zuordnung von Schadenspotenzialen sowie Anhaltswerte für das Wiederkehrintervall

Objektkategorie	Schadenspotenzial	Anhaltswerte für das maßgebende mittlere statistische Wiederkehrintervall T_n[a] a
Sonderobjekte mit außergewöhnlichen Konsequenzen im Hochwasserfall	Hoch	Im Einzelfall zu bestimmen.[b]
Geschlossene Siedlungen	Hoch	etwa 100[b]
Industrieanlagen	Hoch	etwa 100[b]
Überregionale Infrastrukturanlagen	Hoch	etwa 50 bis 100
Einzelgebäude, nicht dauerhaft bewohnte Siedlungen	Mittel	etwa 25
Regionale Infrastrukturanlagen	Mittel	etwa 25
Landwirtschaftlich genutzte Flächen[c]	Gering	bis 5
Naturlandschaften	Gering	—

[a] Die jährliche Eintrittswahrscheinlichkeit entspricht dem reziproken Wert des Wiederkehrintervalls.

[b] In der Praxis sind auch Wiederkehrintervalle bis zu 500 a begründbar und bereits umgesetzt worden.

[c] In der Regel wird eine der Situation angepasste Landwirtschaft betrieben.